Bering Stencil

Designed by **Eugene Yukechev and Dmitry Pilikov (Schrift Foundry)**

Published **2024**

8 styles

OpenType features: **proportional lining figures, fractions, subscript / inferiors, superscript / superiors, 6 stylistic sets**

RUS: Предположительно в 1960-х неизвестный художник из шведского портового городка Шерхамн нарисовал смелый трафаретный леттеринг на спасательном круге. За последующие полвека круг пересёк Балтийское море и оказался в немецком Ростоке, где его и обнаружили авторы Bering.
Bering, построенный по многослойной модульной сетке, переосмыслил и трансформировал идею неизвестного автора, превратив несколько букв в коллекцию из трёх семейств разной ширины. Bering — как и положено трафаретному шрифту — отлично работает в заголовках и небольших текстах на разных поверхностях.
Bering говорит больше чем на 380 языках, среди которых, например, пипиль, распространенный в Сальвадоре, или чама, на котором говорят в Боливии и Перу.

ENG: The origins of Bering can be traced back to a small harbour in the bay near the Swedish city of Skärhamn. The name of that village was stencilled–presumably in the late 1960s–in a very peculiar way on one of the lifebuoys, which was fortunately found by the authors in another harbour in a German city called Rostock.
Bering has a strict, analytical look, bringing to mind the original purpose of the stencil: it was meant to be a simple tool for drawing letters on various surfaces. The design approach, based on a multi-layered modular grid, has made it possible to reinvent the design of the original letterforms. The geometric structure of the typeface also allows the development of the proportions and weights of the type family in various directions.
Bering speaks more than 380 languages, including, for example, Pipil, which is spoken in El Salvador, or the Ese Ejja language, which is spoken in Bolivia and Peru.

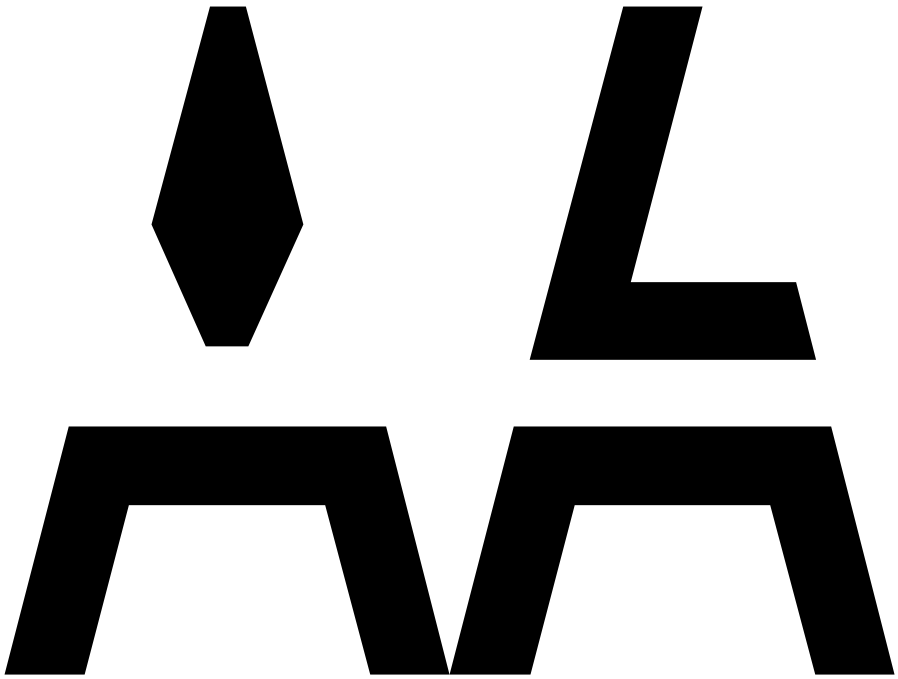

BERING STENCIL CONDENSED THIN
BERING STENCIL CONDENSED LIGHT
BERING STENCIL CONDENSED REGULAR
BERING STENCIL CONDENSED BOLD

BERING STENCIL NARROW THIN
BERING STENCIL NARROW LIGHT
BERING STENCIL NARROW REGULAR
BERING STENCIL NARROW BOLD

BERING STENCIL THIN
BERING STENCIL LIGHT
BERING STENCIL REGULAR
BERING STENCIL BOLD

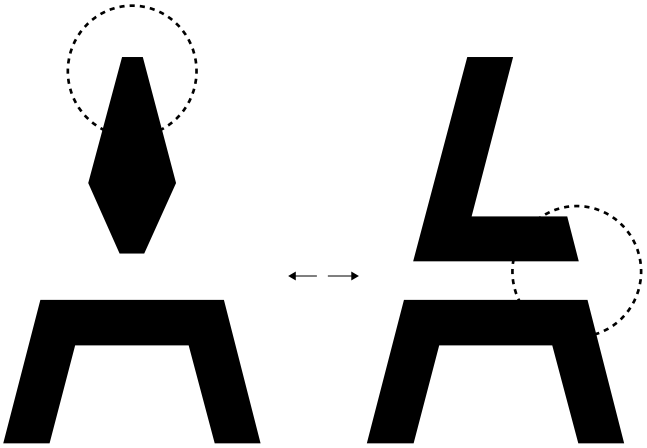

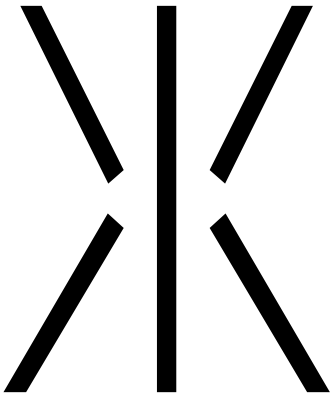

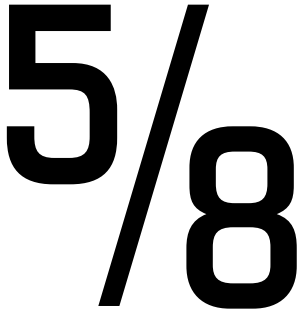

ИТАК, ВСЕ МОИ БЛЕСТЯЩИЕ НАДЕЖДЫ РУШИЛИСЬ!

Bering Stencil Light. 27 pt.

С.-ПЕТЕРБУРГЪ

Bering Stencil Narrow Bold. 88 pt.

SCHRIFTSTELLERISCHEM

Bering Stencil Condensed Thin. 89 pt.

МОСКВА—БУЭНОС-АЙРЕС

Bering Stencil Light. 53 pt.

PUSIÉRONSE A BAILAR A LA SOMBRA

Bering Stencil Bold. 33 pt.

TELEGRAM-АККАУНТ

Bering Stencil Narrow Thin. 89 pt.

MURR GEHEIßEN

Bering Stencil Regular. 79,5 pt.

WORLD

Bering Stencil Light. 211 pt.

Bering Stencil Thin, 6/8,5 pt

GREAT BRITAIN, ALSO KNOWN AS BRITAIN, IS AN ISLAND IN THE NORTH ATLANTIC OFF THE NORTH-WEST COAST OF CONTINENTAL EUROPE. WITH AN AREA OF 209,331 KM² (80,823 SQ MI), IT IS THE LARGEST ISLAND IN EUROPE AND THE NINTH-LARGEST IN THE WORLD. IN 2011 THE ISLAND HAD A POPULATION OF ABOUT 61 MILLION PEOPLE, MAKING IT THE THIRD-MOST POPULOUS ISLAND IN THE WORLD, AFTER JAVA IN INDONESIA AND HONSHU IN JAPAN. IT ACCOUNTS FOR THE MAJORITY OF THE BRITISH ISLES ARCHIPELAGO, ALONG WITH OVER 1,000 SMALLER SURROUNDING ISLANDS, INCLUDING THE ISLAND OF IRELAND TO ITS WEST. THE ISLAND IS PART OF THE UNITED KINGDOM OF GREAT BRITAIN AND NORTHERN IRELAND, CONSTITUTING MOST OF ITS TERRITORY: MOST OF ENGLAND, SCOT-

ГОСУДАРСТВО РАСПОЛАГАЕТСЯ НА БРИТАНСКИХ ОСТРОВАХ (ОСТРОВ ВЕЛИКОБРИТАНИЯ, СЕВЕРО-ВОСТОЧНАЯ ЧАСТЬ ОСТРОВА ИРЛАНДИЯ, А ТАКЖЕ БОЛЬШОЕ КОЛИЧЕСТВО БОЛЕЕ МЕЛКИХ ОСТРОВОВ И АРХИПЕЛАГОВ, СРЕДИ КОТОРЫХ ГЕБРИДСКИЕ, ОРКНЕЙСКИЕ И ШЕТЛАНДСКИЕ ОСТРОВА, АНГЛСИ, АРРАН, УАЙТ) В АТЛАНТИЧЕСКОМ ОКЕАНЕ. ОМЫВАЕТСЯ СЕВЕРНЫМ, ИРЛАНДСКИМ, КЕЛЬТСКИМ И ГЕБРИДСКИМ МОРЯМИ. ЮГО-ВОСТОЧНОЕ ПОБЕРЕЖЬЕ РАСПОЛАГАЕТСЯ ВСЕГО В 35 КМ ОТ СЕВЕРНОГО ПОБЕРЕЖЬЯ ФРАНЦИИ, КОТОРЫЕ РАЗДЕЛЕНЫ ПРОЛИВОМ ЛА-МАНШ. ПЛОЩАДЬ ВЕЛИКОБРИТАНИИ СОСТАВЛЯЕТ 243 809 КМ², ИЗ НИХ СУША — 240 579 КМ², ВНУТРЕННИЕ ВОДЫ — 3230 КМ². ПО ДАННЫМ НА 1993 ГОД 10% СУШИ БЫЛИ ПОКРЫТЫ ЛЕСОМ, 46% ИСПОЛЬЗОВАЛИСЬ

Bering Stencil Thin, 8/10,5 pt

GREAT BRITAIN, ALSO KNOWN AS BRITAIN, IS AN ISLAND IN THE NORTH ATLANTIC OFF THE NORTH-WEST COAST OF CONTINENTAL EUROPE. WITH AN AREA OF 209,331 KM² (80,823 SQ MI), IT IS THE LARGEST ISLAND IN EUROPE AND THE NINTH-LARGEST IN THE WORLD. IN 2011 THE ISLAND HAD A POPULATION OF ABOUT 61 MILLION PEOPLE, MAKING IT THE THIRD-MOST POPULOUS ISLAND IN THE WORLD, AFTER JAVA IN INDONESIA AND HONSHU IN JAPAN. IT ACCOUNTS FOR THE MAJORITY OF THE BRITISH ISLES ARCHIPELAGO,

ГОСУДАРСТВО РАСПОЛАГАЕТСЯ НА БРИТАНСКИХ ОСТРОВАХ (ОСТРОВ ВЕЛИКОБРИТАНИЯ, СЕВЕРО-ВОСТОЧНАЯ ЧАСТЬ ОСТРОВА ИРЛАНДИЯ, А ТАКЖЕ БОЛЬШОЕ КОЛИЧЕСТВО БОЛЕЕ МЕЛКИХ ОСТРОВОВ И АРХИПЕЛАГОВ, СРЕДИ КОТОРЫХ ГЕБРИДСКИЕ, ОРКНЕЙСКИЕ И ШЕТЛАНДСКИЕ ОСТРОВА, АНГЛСИ, АРРАН, УАЙТ) В АТЛАНТИЧЕСКОМ ОКЕАНЕ. ОМЫВАЕТСЯ СЕВЕРНЫМ, ИРЛАНДСКИМ, КЕЛЬТСКИМ И ГЕБРИДСКИМ МОРЯМИ. ЮГО-ВОСТОЧНОЕ ПОБЕРЕЖЬЕ РАСПОЛАГАЕТСЯ ВСЕГО В 35 КМ ОТ СЕВЕРНОГО

Bering Stencil Thin, 10/13,5 pt

GREAT BRITAIN, ALSO KNOWN AS BRITAIN, IS AN ISLAND IN THE NORTH ATLANTIC OFF THE NORTH-WEST COAST OF CONTINENTAL EUROPE. WITH AN AREA OF 209,331 KM² (80,823 SQ MI), IT IS THE LARGEST ISLAND IN EUROPE AND THE NINTH-LARGEST IN THE WORLD. IN 2011 THE ISLAND HAD A POPULATION OF ABOUT 61 MILLION PEOPLE, MAKING IT THE THIRD-MOST POPULOUS ISLAND IN THE WORLD, AFTER JAVA IN INDONESIA AND HONSHU IN JAPAN. IT ACCOUNTS FOR THE MAJORITY OF THE BRITISH ISLES ARCHIPELAGO, ALONG WITH OVER 1,000 SMALLER SURROUNDING ISLANDS, INCLUDING THE ISLAND OF IRELAND TO ITS WEST. THE ISLAND IS PART OF THE UNITED KINGDOM OF GREAT BRITAIN AND NORTHERN IRELAND, CONSTITUTING MOST OF ITS TERRITORY: MOST OF ENGLAND, SCOTLAND, AND WALES ARE ON THE ISLAND, WITH THEIR RESPECTIVE CAPITAL CITIES, LONDON, EDINBURGH, AND CARDIFF. POLITICALLY, THE TERM GREAT BRITAIN USUALLY EXTENDS

ГОСУДАРСТВО РАСПОЛАГАЕТСЯ НА БРИТАНСКИХ ОСТРОВАХ (ОСТРОВ ВЕЛИКОБРИТАНИЯ, СЕВЕРО-ВОСТОЧНАЯ ЧАСТЬ ОСТРОВА ИРЛАНДИЯ, А ТАКЖЕ БОЛЬШОЕ КОЛИЧЕСТВО БОЛЕЕ МЕЛКИХ ОСТРОВОВ И АРХИПЕЛАГОВ, СРЕДИ КОТОРЫХ ГЕБРИДСКИЕ, ОРКНЕЙСКИЕ И ШЕТЛАНДСКИЕ ОСТРОВА, АНГЛСИ, АРРАН, УАЙТ) В АТЛАНТИЧЕСКОМ ОКЕАНЕ. ОМЫВАЕТСЯ СЕВЕРНЫМ, ИРЛАНДСКИМ, КЕЛЬТСКИМ И ГЕБРИДСКИМ МОРЯМИ. ЮГО-ВОСТОЧНОЕ ПОБЕРЕЖЬЕ РАСПОЛАГАЕТСЯ ВСЕГО В 35 КМ ОТ СЕВЕРНОГО ПОБЕРЕЖЬЯ ФРАНЦИИ, КОТОРЫЕ РАЗДЕЛЕНЫ ПРОЛИВОМ ЛА-МАНШ. ПЛОЩАДЬ ВЕЛИКОБРИТАНИИ СОСТАВЛЯЕТ 243 809 КМ², ИЗ НИХ СУША — 240 579 КМ², ВНУТРЕННИЕ ВОДЫ — 3230 КМ². ПО ДАННЫМ НА 1993 ГОД 10% СУШИ БЫЛИ ПОКРЫТЫ ЛЕСОМ, 46% ИСПОЛЬЗОВАЛИСЬ ПОД ПАСТБИЩА, А ЕЩЁ 25% ИСПОЛЬЗОВАЛОСЬ В ЗЕМЛЕДЕЛИИ. ЮЖНОЕ ПОБЕРЕЖЬЕ СОЕДИНЕНО С КОНТИНЕНТАЛЬНОЙ ЕВРОПОЙ ЧЕРЕЗ ЕВРОТОННЕЛЬ ДЛИНОЙ 50 КМ (ИЗ КОТОРЫХ 38 КМ ПОД

Bering Stencil Thin, 12/15,5 pt

GREAT BRITAIN, ALSO KNOWN AS BRITAIN, IS AN ISLAND IN THE NORTH ATLANTIC OFF THE NORTH-WEST COAST OF CONTINENTAL EUROPE. WITH AN AREA OF 209,331 KM² (80,823 SQ MI), IT IS THE LARGEST ISLAND IN EUROPE AND THE NINTH-LARGEST IN THE WORLD. IN 2011 THE ISLAND HAD A POPULATION OF ABOUT 61 MILLION PEOPLE, MAKING IT THE THIRD-MOST POPULOUS ISLAND IN THE WORLD, AFTER JAVA IN INDONESIA AND HONSHU IN JAPAN. IT ACCOUNTS FOR THE MAJORITY OF THE BRITISH ISLES ARCHIPELAGO, ALONG WITH OVER 1,000 SMALLER SURROUNDING ISLANDS, INCLUDING THE ISLAND OF IRELAND TO ITS WEST. THE ISLAND IS PART OF THE UNITED KINGDOM OF GREAT BRITAIN AND NORTHERN

ГОСУДАРСТВО РАСПОЛАГАЕТСЯ НА БРИТАНСКИХ ОСТРОВАХ (ОСТРОВ ВЕЛИКОБРИТАНИЯ, СЕВЕРО-ВОСТОЧНАЯ ЧАСТЬ ОСТРОВА ИРЛАНДИЯ, А ТАКЖЕ БОЛЬШОЕ КОЛИЧЕСТВО БОЛЕЕ МЕЛКИХ ОСТРОВОВ И АРХИПЕЛАГОВ. ОМЫВАЕТСЯ СЕВЕРНЫМ, ИРЛАНДСКИМ, КЕЛЬТСКИМ И ГЕБРИДСКИМ МОРЯМИ. ПЛОЩАДЬ ВЕЛИКОБРИТАНИИ СОСТАВЛЯЕТ 243 809 КМ², ИЗ НИХ СУША — 240 579 КМ², ВНУТРЕННИЕ ВОДЫ — 3230 КМ². ПО ДАННЫМ НА 1993 ГОД 10% СУШИ БЫЛИ ПОКРЫТЫ ЛЕСОМ, 46% ИСПОЛЬЗОВАЛИСЬ ПОД ПАСТБИЩА, А ЕЩЁ 25% ИСПОЛЬЗОВАЛОСЬ В ЗЕМЛЕДЕЛИИ. КАЖДАЯ СТРАНА СОЕДИНЁННОГО КОРОЛЕВСТВА ИМЕЕТ СВОЮ СОБСТВЕННУЮ СИСТЕМУ АДМИНИСТРАТИВНОГО И ГЕОГРАФИЧЕСКОГО ДЕЛЕНИЯ,

Bering Stencil Light, 6/8,5 pt

GREAT BRITAIN, ALSO KNOWN AS BRITAIN, IS AN ISLAND IN THE NORTH ATLANTIC OFF THE NORTH-WEST COAST OF CONTINENTAL EUROPE. WITH AN AREA OF 209,331 KM² (80,823 SQ MI), IT IS THE LARGEST ISLAND IN EUROPE AND THE NINTH-LARGEST IN THE WORLD. IN 2011 THE ISLAND HAD A POPULATION OF ABOUT 61 MILLION PEOPLE, MAKING IT THE THIRD-MOST POPULOUS ISLAND IN THE WORLD, AFTER JAVA IN INDONESIA AND HONSHU IN JAPAN. IT ACCOUNTS FOR THE MAJORITY OF THE BRITISH ISLES ARCHIPELAGO, ALONG WITH OVER 1,000 SMALLER SURROUNDING ISLANDS, INCLUDING THE ISLAND OF IRELAND TO ITS WEST. THE ISLAND IS PART OF THE UNITED KINGDOM OF GREAT BRITAIN AND NORTHERN IRELAND, CONSTITUTING

ГОСУДАРСТВО РАСПОЛАГАЕТСЯ НА БРИТАНСКИХ ОСТРОВАХ (ОСТРОВ ВЕЛИКОБРИТАНИЯ, СЕВЕРО-ВОСТОЧНАЯ ЧАСТЬ ОСТРОВА ИРЛАНДИЯ, А ТАКЖЕ БОЛЬШОЕ КОЛИЧЕСТВО БОЛЕЕ МЕЛКИХ ОСТРОВОВ И АРХИПЕЛАГОВ, СРЕДИ КОТОРЫХ ГЕБРИДСКИЕ, ОРКНЕЙСКИЕ И ШЕТЛАНДСКИЕ ОСТРОВА, АНГЛСИ, АРРАН, УАЙТ) В АТЛАНТИЧЕСКОМ ОКЕАНЕ. ОМЫВАЕТСЯ СЕВЕРНЫМ, ИРЛАНДСКИМ, КЕЛЬТСКИМ И ГЕБРИДСКИМ МОРЯМИ. ЮГО-ВОСТОЧНОЕ ПОБЕРЕЖЬЕ РАСПОЛАГАЕТСЯ ВСЕГО В 35 КМ ОТ СЕВЕРНОГО ПОБЕРЕЖЬЯ ФРАНЦИИ, КОТОРЫЕ РАЗДЕЛЕНЫ ПРОЛИВОМ ЛА-МАНШ. ПЛОЩАДЬ ВЕЛИКОБРИТАНИИ СОСТАВЛЯЕТ 243 809 КМ², ИЗ НИХ СУША — 240 579 КМ², ВНУТРЕННИЕ ВОДЫ — 3230 КМ². ПО ДАННЫМ НА 1993

Bering Stencil Light, 8/10,5 pt

GREAT BRITAIN, ALSO KNOWN AS BRITAIN, IS AN ISLAND IN THE NORTH ATLANTIC OFF THE NORTH-WEST COAST OF CONTINENTAL EUROPE. WITH AN AREA OF 209,331 KM² (80,823 SQ MI), IT IS THE LARGEST ISLAND IN EUROPE AND THE NINTH-LARGEST IN THE WORLD. IN 2011 THE ISLAND HAD A POPULATION OF ABOUT 61 MILLION PEOPLE, MAKING IT THE THIRD-MOST POPULOUS ISLAND IN THE WORLD, AFTER JAVA IN INDONESIA AND HONSHU IN JAPAN. IT ACCOUNTS FOR THE

ГОСУДАРСТВО РАСПОЛАГАЕТСЯ НА БРИТАНСКИХ ОСТРОВАХ (ОСТРОВ ВЕЛИКОБРИТАНИЯ, СЕВЕРО-ВОСТОЧНАЯ ЧАСТЬ ОСТРОВА ИРЛАНДИЯ, А ТАКЖЕ БОЛЬШОЕ КОЛИЧЕСТВО БОЛЕЕ МЕЛКИХ ОСТРОВОВ И АРХИПЕЛАГОВ, СРЕДИ КОТОРЫХ ГЕБРИДСКИЕ, ОРКНЕЙСКИЕ И ШЕТЛАНДСКИЕ ОСТРОВА, АНГЛСИ, АРРАН, УАЙТ) В АТЛАНТИЧЕСКОМ ОКЕАНЕ. ОМЫВАЕТСЯ СЕВЕРНЫМ, ИРЛАНДСКИМ, КЕЛЬТСКИМ И ГЕБРИДСКИМ МОРЯМИ. ЮГО-ВОСТОЧНОЕ ПОБЕРЕЖЬЕ РАСПОЛАГАЕТСЯ ВСЕГО В 35

Bering Stencil Light, 10/13,5 pt

GREAT BRITAIN, ALSO KNOWN AS BRITAIN, IS AN ISLAND IN THE NORTH ATLANTIC OFF THE NORTH-WEST COAST OF CONTINENTAL EUROPE. WITH AN AREA OF 209,331 KM² (80,823 SQ MI), IT IS THE LARGEST ISLAND IN EUROPE AND THE NINTH-LARGEST IN THE WORLD. IN 2011 THE ISLAND HAD A POPULATION OF ABOUT 61 MILLION PEOPLE, MAKING IT THE THIRD-MOST POPULOUS ISLAND IN THE WORLD, AFTER JAVA IN INDONESIA AND HONSHU IN JAPAN. IT ACCOUNTS FOR THE MAJORITY OF THE BRITISH ISLES ARCHIPELAGO, ALONG WITH OVER 1,000 SMALLER SURROUNDING ISLANDS, INCLUDING THE ISLAND OF IRELAND TO ITS WEST. THE ISLAND IS PART OF THE UNITED KINGDOM OF GREAT BRITAIN AND NORTHERN IRELAND, CONSTITUTING MOST OF ITS TERRITORY: MOST OF ENGLAND, SCOTLAND, AND WALES ARE ON THE ISLAND, WITH THEIR RESPECTIVE CAPITAL CITIES,

ГОСУДАРСТВО РАСПОЛАГАЕТСЯ НА БРИТАНСКИХ ОСТРОВАХ (ОСТРОВ ВЕЛИКОБРИТАНИЯ, СЕВЕРО-ВОСТОЧНАЯ ЧАСТЬ ОСТРОВА ИРЛАНДИЯ, А ТАКЖЕ БОЛЬШОЕ КОЛИЧЕСТВО БОЛЕЕ МЕЛКИХ ОСТРОВОВ И АРХИПЕЛАГОВ, СРЕДИ КОТОРЫХ ГЕБРИДСКИЕ, ОРКНЕЙСКИЕ И ШЕТЛАНДСКИЕ ОСТРОВА, АНГЛСИ, АРРАН, УАЙТ) В АТЛАНТИЧЕСКОМ ОКЕАНЕ. ОМЫВАЕТСЯ СЕВЕРНЫМ, ИРЛАНДСКИМ, КЕЛЬТСКИМ И ГЕБРИДСКИМ МОРЯМИ. ЮГО-ВОСТОЧНОЕ ПОБЕРЕЖЬЕ РАСПОЛАГАЕТСЯ ВСЕГО В 35 КМ ОТ СЕВЕРНОГО ПОБЕРЕЖЬЯ ФРАНЦИИ, КОТОРЫЕ РАЗДЕЛЕНЫ ПРОЛИВОМ ЛА-МАНШ. ПЛОЩАДЬ ВЕЛИКОБРИТАНИИ СОСТАВЛЯЕТ 243 809 КМ², ИЗ НИХ СУША — 240 579 КМ², ВНУТРЕННИЕ ВОДЫ — 3230 КМ². ПО ДАННЫМ НА 1993 ГОД 10% СУШИ БЫЛИ ПОКРЫТЫ ЛЕСОМ, 46% ИСПОЛЬЗОВАЛИСЬ ПОД ПАСТБИЩА, А ЕЩЁ 25% ИСПОЛЬЗОВАЛОСЬ В ЗЕМЛЕДЕЛИИ. ЮЖНОЕ ПОБЕРЕЖЬЕ СОЕДИНЕНО С КОНТИНЕНТАЛЬНОЙ ЕВРОПОЙ ЧЕРЕЗ

Bering Stencil Light, 12/15,5 pt

GREAT BRITAIN, ALSO KNOWN AS BRITAIN, IS AN ISLAND IN THE NORTH ATLANTIC OFF THE NORTH-WEST COAST OF CONTINENTAL EUROPE. WITH AN AREA OF 209,331 KM² (80,823 SQ MI), IT IS THE LARGEST ISLAND IN EUROPE AND THE NINTH-LARGEST IN THE WORLD. IN 2011 THE ISLAND HAD A POPULATION OF ABOUT 61 MILLION PEOPLE, MAKING IT THE THIRD-MOST POPULOUS ISLAND IN THE WORLD, AFTER JAVA IN INDONESIA AND HONSHU IN JAPAN. IT ACCOUNTS FOR THE MAJORITY OF THE BRITISH ISLES ARCHIPELAGO, ALONG WITH OVER 1,000 SMALLER SURROUNDING ISLANDS, INCLUDING THE ISLAND OF IRELAND TO ITS WEST. THE ISLAND IS PART OF THE

ГОСУДАРСТВО РАСПОЛАГАЕТСЯ НА БРИТАНСКИХ ОСТРОВАХ (ОСТРОВ ВЕЛИКОБРИТАНИЯ, СЕВЕРО-ВОСТОЧНАЯ ЧАСТЬ ОСТРОВА ИРЛАНДИЯ, А ТАКЖЕ БОЛЬШОЕ КОЛИЧЕСТВО БОЛЕЕ МЕЛКИХ ОСТРОВОВ И АРХИПЕЛАГОВ. ОМЫВАЕТСЯ СЕВЕРНЫМ, ИРЛАНДСКИМ, КЕЛЬТСКИМ И ГЕБРИДСКИМ МОРЯМИ. ПЛОЩАДЬ ВЕЛИКОБРИТАНИИ СОСТАВЛЯЕТ 243 809 КМ², ИЗ НИХ СУША — 240 579 КМ², ВНУТРЕННИЕ ВОДЫ — 3230 КМ². ПО ДАННЫМ НА 1993 ГОД 10% СУШИ БЫЛИ ПОКРЫТЫ ЛЕСОМ, 46% ИСПОЛЬЗОВАЛИСЬ ПОД ПАСТБИЩА, А ЕЩЁ 25% ИСПОЛЬЗОВАЛОСЬ В ЗЕМЛЕДЕЛИИ. КАЖДАЯ СТРАНА СОЕДИНЁННОГО КОРОЛЕВСТВА ИМЕЕТ СВОЮ СОБСТВЕННУЮ

Bering Stencil Regular, 6/8,5 pt

GREAT BRITAIN, ALSO KNOWN AS BRITAIN, IS AN ISLAND IN THE NORTH ATLANTIC OFF THE NORTH-WEST COAST OF CONTINENTAL EUROPE. WITH AN AREA OF 209,331 KM² (80,823 SQ MI), IT IS THE LARGEST ISLAND IN EUROPE AND THE NINTH-LARGEST IN THE WORLD. IN 2011 THE ISLAND HAD A POPULATION OF ABOUT 61 MILLION PEOPLE, MAKING IT THE THIRD-MOST POPULOUS ISLAND IN THE WORLD, AFTER JAVA IN INDONESIA AND HONSHU IN JAPAN. IT ACCOUNTS FOR THE MAJORITY OF THE BRITISH ISLES ARCHIPELAGO, ALONG WITH OVER 1,000 SMALLER SURROUNDING ISLANDS, INCLUDING THE ISLAND OF IRELAND TO ITS WEST. THE ISLAND IS PART OF THE UNITED KINGDOM OF GREAT BRITAIN

ГОСУДАРСТВО РАСПОЛАГАЕТСЯ НА БРИТАНСКИХ ОСТРОВАХ (ОСТРОВ ВЕЛИКОБРИТАНИЯ, СЕВЕРО-ВОСТОЧНАЯ ЧАСТЬ ОСТРОВА ИРЛАНДИЯ, А ТАКЖЕ БОЛЬШОЕ КОЛИЧЕСТВО БОЛЕЕ МЕЛКИХ ОСТРОВОВ И АРХИПЕЛАГОВ, СРЕДИ КОТОРЫХ ГЕБРИДСКИЕ, ОРКНЕЙСКИЕ И ШЕТЛАНДСКИЕ ОСТРОВА, АНГЛСИ, АРРАН, УАЙТ) В АТЛАНТИЧЕСКОМ ОКЕАНЕ. ОМЫВАЕТСЯ СЕВЕРНЫМ, ИРЛАНДСКИМ, КЕЛЬТСКИМ И ГЕБРИДСКИМ МОРЯМИ. ЮГО-ВОСТОЧНОЕ ПОБЕРЕЖЬЕ РАСПОЛАГАЕТСЯ ВСЕГО В 35 КМ ОТ СЕВЕРНОГО ПОБЕРЕЖЬЯ ФРАНЦИИ, КОТОРЫЕ РАЗДЕЛЕНЫ ПРОЛИВОМ ЛА-МАНШ. ПЛОЩАДЬ ВЕЛИКОБРИТАНИИ СОСТАВЛЯЕТ 243 809 КМ², ИЗ НИХ СУША — 240 579 КМ², ВНУТРЕННИЕ

Bering Stencil Regular, 8/10,5 pt

GREAT BRITAIN, ALSO KNOWN AS BRITAIN, IS AN ISLAND IN THE NORTH ATLANTIC OFF THE NORTH-WEST COAST OF CONTINENTAL EUROPE. WITH AN AREA OF 209,331 KM² (80,823 SQ MI), IT IS THE LARGEST ISLAND IN EUROPE AND THE NINTH-LARGEST IN THE WORLD. IN 2011 THE ISLAND HAD A POPULATION OF ABOUT 61 MILLION PEOPLE, MAKING IT THE THIRD-MOST POPULOUS ISLAND IN THE WORLD, AFTER JAVA IN INDONESIA AND HONSHU IN JAPAN. IT ACCOUNTS

ГОСУДАРСТВО РАСПОЛАГАЕТСЯ НА БРИТАНСКИХ ОСТРОВАХ (ОСТРОВ ВЕЛИКОБРИТАНИЯ, СЕВЕРО-ВОСТОЧНАЯ ЧАСТЬ ОСТРОВА ИРЛАНДИЯ, А ТАКЖЕ БОЛЬШОЕ КОЛИЧЕСТВО БОЛЕЕ МЕЛКИХ ОСТРОВОВ И АРХИПЕЛАГОВ, СРЕДИ КОТОРЫХ ГЕБРИДСКИЕ, ОРКНЕЙСКИЕ И ШЕТЛАНДСКИЕ ОСТРОВА, АНГЛСИ, АРРАН, УАЙТ) В АТЛАНТИЧЕСКОМ ОКЕАНЕ. ОМЫВАЕТСЯ СЕВЕРНЫМ, ИРЛАНДСКИМ, КЕЛЬТСКИМ И ГЕБРИДСКИМ МОРЯМИ. ЮГО-ВОСТОЧНОЕ ПОБЕРЕЖЬЕ

Bering Stencil Regular, 10/13,5 pt

GREAT BRITAIN, ALSO KNOWN AS BRITAIN, IS AN ISLAND IN THE NORTH ATLANTIC OFF THE NORTH-WEST COAST OF CONTINENTAL EUROPE. WITH AN AREA OF 209,331 KM² (80,823 SQ MI), IT IS THE LARGEST ISLAND IN EUROPE AND THE NINTH-LARGEST IN THE WORLD. IN 2011 THE ISLAND HAD A POPULATION OF ABOUT 61 MILLION PEOPLE, MAKING IT THE THIRD-MOST POPULOUS ISLAND IN THE WORLD, AFTER JAVA IN INDONESIA AND HONSHU IN JAPAN. IT ACCOUNTS FOR THE MAJORITY OF THE BRITISH ISLES ARCHIPELAGO, ALONG WITH OVER 1,000 SMALLER SURROUNDING ISLANDS, INCLUDING THE ISLAND OF IRELAND TO ITS WEST. THE ISLAND IS PART OF THE UNITED KINGDOM OF GREAT BRITAIN AND NORTHERN IRELAND, CONSTITUTING MOST OF ITS TERRITORY: MOST OF ENGLAND, SCOTLAND, AND WALES ARE ON

ГОСУДАРСТВО РАСПОЛАГАЕТСЯ НА БРИТАНСКИХ ОСТРОВАХ (ОСТРОВ ВЕЛИКОБРИТАНИЯ, СЕВЕРО-ВОСТОЧНАЯ ЧАСТЬ ОСТРОВА ИРЛАНДИЯ, А ТАКЖЕ БОЛЬШОЕ КОЛИЧЕСТВО БОЛЕЕ МЕЛКИХ ОСТРОВОВ И АРХИПЕЛАГОВ, СРЕДИ КОТОРЫХ ГЕБРИДСКИЕ, ОРКНЕЙСКИЕ И ШЕТЛАНДСКИЕ ОСТРОВА, АНГЛСИ, АРРАН, УАЙТ) В АТЛАНТИЧЕСКОМ ОКЕАНЕ. ОМЫВАЕТСЯ СЕВЕРНЫМ, ИРЛАНДСКИМ, КЕЛЬТСКИМ И ГЕБРИДСКИМ МОРЯМИ. ЮГО-ВОСТОЧНОЕ ПОБЕРЕЖЬЕ РАСПОЛАГАЕТСЯ ВСЕГО В 35 КМ ОТ СЕВЕРНОГО ПОБЕРЕЖЬЯ ФРАНЦИИ, КОТОРЫЕ РАЗДЕЛЕНЫ ПРОЛИВОМ ЛА-МАНШ. ПЛОЩАДЬ ВЕЛИКОБРИТАНИИ СОСТАВЛЯЕТ 243 809 КМ², ИЗ НИХ СУША — 240 579 КМ², ВНУТРЕННИЕ ВОДЫ — 3230 КМ². ПО ДАННЫМ НА 1993 ГОД 10% СУШИ БЫЛИ ПОКРЫТЫ ЛЕСОМ, 46% ИСПОЛЬЗОВАЛИСЬ ПОД ПАСТБИЩА, А ЕЩЁ 25% ИСПОЛЬЗОВАЛОСЬ В ЗЕМЛЕДЕЛИИ.

Bering Stencil Regular, 12/15,5 pt

GREAT BRITAIN, ALSO KNOWN AS BRITAIN, IS AN ISLAND IN THE NORTH ATLANTIC OFF THE NORTH-WEST COAST OF CONTINENTAL EUROPE. WITH AN AREA OF 209,331 KM² (80,823 SQ MI), IT IS THE LARGEST ISLAND IN EUROPE AND THE NINTH-LARGEST IN THE WORLD. IN 2011 THE ISLAND HAD A POPULATION OF ABOUT 61 MILLION PEOPLE, MAKING IT THE THIRD-MOST POPULOUS ISLAND IN THE WORLD, AFTER JAVA IN INDONESIA AND HONSHU IN JAPAN. IT ACCOUNTS FOR THE MAJORITY OF THE BRITISH ISLES ARCHIPELAGO, ALONG WITH OVER 1,000 SMALLER SURROUNDING ISLANDS, INCLUDING THE ISLAND OF IRELAND

ГОСУДАРСТВО РАСПОЛАГАЕТСЯ НА БРИТАНСКИХ ОСТРОВАХ (ОСТРОВ ВЕЛИКОБРИТАНИЯ, СЕВЕРО-ВОСТОЧНАЯ ЧАСТЬ ОСТРОВА ИРЛАНДИЯ, А ТАКЖЕ БОЛЬШОЕ КОЛИЧЕСТВО БОЛЕЕ МЕЛКИХ ОСТРОВОВ И АРХИПЕЛАГОВ. ОМЫВАЕТСЯ СЕВЕРНЫМ, ИРЛАНДСКИМ, КЕЛЬТСКИМ И ГЕБРИДСКИМ МОРЯМИ. ПЛОЩАДЬ ВЕЛИКОБРИТАНИИ СОСТАВЛЯЕТ 243 809 КМ², ИЗ НИХ СУША — 240 579 КМ², ВНУТРЕННИЕ ВОДЫ — 3230 КМ². ПО ДАННЫМ НА 1993 ГОД 10% СУШИ БЫЛИ ПОКРЫТЫ ЛЕСОМ, 46% ИСПОЛЬЗОВАЛИСЬ ПОД ПАСТБИЩА, А ЕЩЁ 25% ИСПОЛЬЗОВАЛОСЬ В ЗЕМЛЕДЕЛИИ. КАЖДАЯ СТРАНА СОЕДИНЁННОГО КОРОЛЕВСТВА ИМЕЕТ СВОЮ

Bering Stencil Bold, 6/8,5 pt

GREAT BRITAIN, ALSO KNOWN AS BRITAIN, IS AN ISLAND IN THE NORTH ATLANTIC OFF THE NORTH-WEST COAST OF CONTINENTAL EUROPE. WITH AN AREA OF 209,331 KM² (80,823 SQ MI), IT IS THE LARGEST ISLAND IN EUROPE AND THE NINTH-LARGEST IN THE WORLD. IN 2011 THE ISLAND HAD A POPULATION OF ABOUT 61 MILLION PEOPLE, MAKING IT THE THIRD-MOST POPULOUS ISLAND IN THE WORLD, AFTER JAVA IN INDONESIA AND HONSHU IN JAPAN. IT ACCOUNTS FOR THE MAJORITY OF THE BRITISH ISLES ARCHIPELAGO, ALONG WITH OVER 1,000 SMALLER SURROUNDING ISLANDS, INCLUDING THE ISLAND OF IRELAND TO ITS WEST. THE ISLAND

ГОСУДАРСТВО РАСПОЛАГАЕТСЯ НА БРИТАНСКИХ ОСТРОВАХ (ОСТРОВ ВЕЛИКОБРИТАНИЯ, СЕВЕРО-ВОСТОЧНАЯ ЧАСТЬ ОСТРОВА ИРЛАНДИЯ, А ТАКЖЕ БОЛЬШОЕ КОЛИЧЕСТВО БОЛЕЕ МЕЛКИХ ОСТРОВОВ И АРХИПЕЛАГОВ, СРЕДИ КОТОРЫХ ГЕБРИДСКИЕ, ОРКНЕЙСКИЕ И ШЕТЛАНДСКИЕ ОСТРОВА, АНГЛСИ, АРРАН, УАЙТ) В АТЛАНТИЧЕСКОМ ОКЕАНЕ. ОМЫВАЕТСЯ СЕВЕРНЫМ, ИРЛАНДСКИМ, КЕЛЬТСКИМ И ГЕБРИДСКИМ МОРЯМИ. ЮГО-ВОСТОЧНОЕ ПОБЕРЕЖЬЕ РАСПОЛАГАЕТСЯ ВСЕГО В 35 КМ ОТ СЕВЕРНОГО ПОБЕРЕЖЬЯ ФРАНЦИИ, КОТОРЫЕ РАЗДЕЛЕНЫ ПРОЛИВОМ ЛА-МАНШ. ПЛОЩАДЬ ВЕЛИКОБРИТАНИИ СОСТАВЛЯЕТ 243 809 КМ², ИЗ НИХ

Bering Stencil Bold, 8/10,5 pt

GREAT BRITAIN, ALSO KNOWN AS BRITAIN, IS AN ISLAND IN THE NORTH ATLANTIC OFF THE NORTH-WEST COAST OF CONTINENTAL EUROPE. WITH AN AREA OF 209,331 KM² (80,823 SQ MI), IT IS THE LARGEST ISLAND IN EUROPE AND THE NINTH-LARGEST IN THE WORLD. IN 2011 THE ISLAND HAD A POPULATION OF ABOUT 61 MILLION PEOPLE, MAKING IT THE THIRD-MOST POPULOUS ISLAND IN THE WORLD, AFTER JAVA IN

ГОСУДАРСТВО РАСПОЛАГАЕТСЯ НА БРИТАНСКИХ ОСТРОВАХ (ОСТРОВ ВЕЛИКОБРИТАНИЯ, СЕВЕРО-ВОСТОЧНАЯ ЧАСТЬ ОСТРОВА ИРЛАНДИЯ, А ТАКЖЕ БОЛЬШОЕ КОЛИЧЕСТВО БОЛЕЕ МЕЛКИХ ОСТРОВОВ И АРХИПЕЛАГОВ, СРЕДИ КОТОРЫХ ГЕБРИДСКИЕ, ОРКНЕЙСКИЕ И ШЕТЛАНДСКИЕ ОСТРОВА, АНГЛСИ, АРРАН, УАЙТ) В АТЛАНТИЧЕСКОМ ОКЕАНЕ. ОМЫВАЕТСЯ СЕВЕРНЫМ, ИРЛАНДСКИМ, КЕЛЬТСКИМ И ГЕ-

Bering Stencil Bold, 10/13,5 pt

GREAT BRITAIN, ALSO KNOWN AS BRITAIN, IS AN ISLAND IN THE NORTH ATLANTIC OFF THE NORTH-WEST COAST OF CONTINENTAL EUROPE. WITH AN AREA OF 209,331 KM² (80,823 SQ MI), IT IS THE LARGEST ISLAND IN EUROPE AND THE NINTH-LARGEST IN THE WORLD. IN 2011 THE ISLAND HAD A POPULATION OF ABOUT 61 MILLION PEOPLE, MAKING IT THE THIRD-MOST POPULOUS ISLAND IN THE WORLD, AFTER JAVA IN INDONESIA AND HONSHU IN JAPAN. IT ACCOUNTS FOR THE MAJORITY OF THE BRITISH ISLES ARCHIPELAGO, ALONG WITH OVER 1,000 SMALLER SURROUNDING ISLANDS, INCLUDING THE ISLAND OF IRELAND TO ITS WEST. THE ISLAND IS PART OF THE UNITED KINGDOM OF GREAT BRITAIN AND NORTHERN IRELAND, CONSTITUTING MOST OF ITS TERRITORY:

ГОСУДАРСТВО РАСПОЛАГАЕТСЯ НА БРИТАНСКИХ ОСТРОВАХ (ОСТРОВ ВЕЛИКОБРИТАНИЯ, СЕВЕРО-ВОСТОЧНАЯ ЧАСТЬ ОСТРОВА ИРЛАНДИЯ, А ТАКЖЕ БОЛЬШОЕ КОЛИЧЕСТВО БОЛЕЕ МЕЛКИХ ОСТРОВОВ И АРХИПЕЛАГОВ, СРЕДИ КОТОРЫХ ГЕБРИДСКИЕ, ОРКНЕЙСКИЕ И ШЕТЛАНДСКИЕ ОСТРОВА, АНГЛСИ, АРРАН, УАЙТ) В АТЛАНТИЧЕСКОМ ОКЕАНЕ. ОМЫВАЕТСЯ СЕВЕРНЫМ, ИРЛАНДСКИМ, КЕЛЬТСКИМ И ГЕБРИДСКИМ МОРЯМИ. ЮГО-ВОСТОЧНОЕ ПОБЕРЕЖЬЕ РАСПОЛАГАЕТСЯ ВСЕГО В 35 КМ ОТ СЕВЕРНОГО ПОБЕРЕЖЬЯ ФРАНЦИИ, КОТОРЫЕ РАЗДЕЛЕНЫ ПРОЛИВОМ ЛА-МАНШ. ПЛОЩАДЬ ВЕЛИКОБРИТАНИИ СОСТАВЛЯЕТ 243 809 КМ², ИЗ НИХ СУША — 240 579 КМ², ВНУТРЕННИЕ ВОДЫ — 3230 КМ². ПО ДАННЫМ НА 1993 ГОД 10% СУШИ БЫЛИ ПОКРЫТЫ ЛЕСОМ, 46% ИСПОЛЬЗОВАЛИСЬ ПОД ПАСТБИ-

Bering Stencil Bold, 12/15,5 pt

GREAT BRITAIN, ALSO KNOWN AS BRITAIN, IS AN ISLAND IN THE NORTH ATLANTIC OFF THE NORTH-WEST COAST OF CONTINENTAL EUROPE. WITH AN AREA OF 209,331 KM² (80,823 SQ MI), IT IS THE LARGEST ISLAND IN EUROPE AND THE NINTH-LARGEST IN THE WORLD. IN 2011 THE ISLAND HAD A POPULATION OF ABOUT 61 MILLION PEOPLE, MAKING IT THE THIRD-MOST POPULOUS ISLAND IN THE WORLD, AFTER JAVA IN INDONESIA AND HONSHU IN JAPAN. IT ACCOUNTS FOR THE MAJORITY OF THE BRITISH ISLES ARCHIPELAGO, ALONG WITH OVER 1,000 SMALLER SURROUNDING

ГОСУДАРСТВО РАСПОЛАГАЕТСЯ НА БРИТАНСКИХ ОСТРОВАХ (ОСТРОВ ВЕЛИКОБРИТАНИЯ, СЕВЕРО-ВОСТОЧНАЯ ЧАСТЬ ОСТРОВА ИРЛАНДИЯ, А ТАКЖЕ БОЛЬШОЕ КОЛИЧЕСТВО БОЛЕЕ МЕЛКИХ ОСТРОВОВ И АРХИПЕЛАГОВ. ОМЫВАЕТСЯ СЕВЕРНЫМ, ИРЛАНДСКИМ, КЕЛЬТСКИМ И ГЕБРИДСКИМ МОРЯМИ. ПЛОЩАДЬ ВЕЛИКОБРИТАНИИ СОСТАВЛЯЕТ 243 809 КМ², ИЗ НИХ СУША — 240 579 КМ², ВНУТРЕННИЕ ВОДЫ — 3230 КМ². ПО ДАННЫМ НА 1993 ГОД 10% СУШИ БЫЛИ ПОКРЫТЫ ЛЕСОМ, 46% ИСПОЛЬЗОВАЛИСЬ ПОД ПАСТБИЩА, А ЕЩЁ 25% ИСПОЛЬЗОВАЛОСЬ В ЗЕМЛЕДЕЛИИ. КАЖДАЯ

Bering Stencil Light, Bold,
6/8,5 pt

GREAT BRITAIN, ALSO KNOWN AS BRITAIN, IS AN ISLAND IN THE NORTH ATLANTIC OFF THE NORTH-WEST COAST OF CONTINENTAL EUROPE. WITH AN AREA OF 209,331 KM² (80,823 SQ MI), IT IS THE LARGEST ISLAND IN EUROPE AND THE NINTH-LARGEST IN THE WORLD. **IN 2011 THE ISLAND HAD A POPULATION OF ABOUT 61 MILLION PEOPLE, MAKING IT THE THIRD-MOST POPULOUS ISLAND IN THE WORLD, AFTER JAVA IN INDONESIA AND HONSHU IN JAPAN.** IT ACCOUNTS FOR THE MAJORITY OF THE BRITISH ISLES ARCHIPELAGO, ALONG WITH OVER 1,000 SMALLER SURROUNDING ISLANDS, INCLUDING THE ISLAND OF IRELAND TO ITS WEST. THE ISLAND IS PART OF THE UNITED KINGDOM OF GREAT BRITAIN AND NORTHERN

ГОСУДАРСТВО РАСПОЛАГАЕТСЯ НА БРИТАНСКИХ ОСТРОВАХ (ОСТРОВ ВЕЛИКОБРИТАНИЯ, СЕВЕРО-ВОСТОЧНАЯ ЧАСТЬ ОСТРОВА ИРЛАНДИЯ, А ТАКЖЕ БОЛЬШОЕ КОЛИЧЕСТВО БОЛЕЕ МЕЛКИХ ОСТРОВОВ И АРХИПЕЛАГОВ, СРЕДИ КОТОРЫХ ГЕБРИДСКИЕ, ОРКНЕЙСКИЕ И ШЕТЛАНДСКИЕ ОСТРОВА, АНГЛСИ, АРРАН, УАЙТ) В АТЛАНТИЧЕСКОМ ОКЕАНЕ. **ОМЫВАЕТСЯ СЕВЕРНЫМ, ИРЛАНДСКИМ, КЕЛЬТСКИМ И ГЕБРИДСКИМ МОРЯМИ.** ЮГО-ВОСТОЧНОЕ ПОБЕРЕЖЬЕ РАСПОЛАГАЕТСЯ ВСЕГО В 35 КМ ОТ СЕВЕРНОГО ПОБЕРЕЖЬЯ ФРАНЦИИ, КОТОРЫЕ РАЗДЕЛЕНЫ ПРОЛИВОМ ЛА-МАНШ. ПЛОЩАДЬ ВЕЛИКОБРИТАНИИ СОСТАВЛЯЕТ 243 809 КМ², ИЗ НИХ СУША — 240 579 КМ², ВНУТРЕННИЕ ВОДЫ — 3230 КМ². ПО ДАННЫМ НА 1993

Bering Stencil Light, Bold,
8/10,5 pt

GREAT BRITAIN, ALSO KNOWN AS BRITAIN, IS AN ISLAND IN THE NORTH ATLANTIC OFF THE NORTH-WEST COAST OF CONTINENTAL EUROPE. WITH AN AREA OF 209,331 KM² (80,823 SQ MI), **IT IS THE LARGEST ISLAND IN EUROPE AND THE NINTH-LARGEST IN THE WORLD.** IN 2011 THE ISLAND HAD A POPULATION OF ABOUT 61 MILLION PEOPLE, MAKING IT THE THIRD-MOST POPULOUS ISLAND IN THE WORLD, AFTER JAVA IN INDONESIA AND HONSHU IN JAPAN. IT ACCOUNTS FOR THE

ГОСУДАРСТВО РАСПОЛАГАЕТСЯ НА БРИТАНСКИХ ОСТРОВАХ (ОСТРОВ ВЕЛИКОБРИТАНИЯ, СЕВЕРО-ВОСТОЧНАЯ ЧАСТЬ ОСТРОВА ИРЛАНДИЯ, **А ТАКЖЕ БОЛЬШОЕ КОЛИЧЕСТВО БОЛЕЕ МЕЛКИХ ОСТРОВОВ И АРХИПЕЛАГОВ,** СРЕДИ КОТОРЫХ ГЕБРИДСКИЕ, ОРКНЕЙСКИЕ И ШЕТЛАНДСКИЕ ОСТРОВА, АНГЛСИ, АРРАН, УАЙТ) В АТЛАНТИЧЕСКОМ ОКЕАНЕ. ОМЫВАЕТСЯ СЕВЕРНЫМ, ИРЛАНДСКИМ, КЕЛЬТСКИМ И ГЕБРИДСКИМ МОРЯМИ. ЮГО-ВОСТОЧНОЕ ПОБЕРЕЖЬЕ РАСПОЛАГАЕТСЯ ВСЕГО

Bering Stencil Light, Bold,
10/13,5 pt

GREAT BRITAIN, ALSO KNOWN AS BRITAIN, IS AN ISLAND IN THE NORTH ATLANTIC OFF THE NORTH-WEST COAST OF CONTINENTAL EUROPE. WITH AN AREA OF 209,331 KM² (80,823 SQ MI), IT IS THE LARGEST ISLAND IN EUROPE AND THE NINTH-LARGEST IN THE WORLD. IN 2011 THE ISLAND HAD A POPULATION OF ABOUT 61 MILLION PEOPLE, MAKING IT THE THIRD-MOST POPULOUS ISLAND IN THE WORLD, AFTER JAVA IN INDONESIA AND HONSHU IN JAPAN. **IT ACCOUNTS FOR THE MAJORITY OF THE BRITISH ISLES ARCHIPELAGO, ALONG WITH OVER 1,000 SMALLER SURROUNDING ISLANDS, INCLUDING THE ISLAND OF IRELAND TO ITS WEST.** THE ISLAND IS PART OF THE UNITED KINGDOM OF GREAT BRITAIN AND NORTHERN IRELAND, CONSTITUTING MOST OF ITS TERRITORY: MOST OF ENGLAND, SCOTLAND, AND WALES ARE ON THE ISLAND, WITH THEIR RESPECTIVE

ГОСУДАРСТВО РАСПОЛАГАЕТСЯ НА БРИТАНСКИХ ОСТРОВАХ (ОСТРОВ ВЕЛИКОБРИТАНИЯ, СЕВЕРО-ВОСТОЧНАЯ ЧАСТЬ ОСТРОВА ИРЛАНДИЯ, А ТАКЖЕ БОЛЬШОЕ КОЛИЧЕСТВО БОЛЕЕ МЕЛКИХ ОСТРОВОВ И АРХИПЕЛАГОВ, СРЕДИ КОТОРЫХ ГЕБРИДСКИЕ, ОРКНЕЙСКИЕ И ШЕТЛАНДСКИЕ ОСТРОВА, АНГЛСИ, АРРАН, УАЙТ) В АТЛАНТИЧЕСКОМ ОКЕАНЕ. ОМЫВАЕТСЯ СЕВЕРНЫМ, ИРЛАНДСКИМ, КЕЛЬТСКИМ И ГЕБРИДСКИМ МОРЯМИ. **ЮГО-ВОСТОЧНОЕ ПОБЕРЕЖЬЕ РАСПОЛАГАЕТСЯ ВСЕГО В 35 КМ ОТ СЕВЕРНОГО ПОБЕРЕЖЬЯ ФРАНЦИИ, КОТОРЫЕ РАЗДЕЛЕНЫ ПРОЛИВОМ ЛА-МАНШ.** ПЛОЩАДЬ ВЕЛИКОБРИТАНИИ СОСТАВЛЯЕТ 243 809 КМ², ИЗ НИХ СУША — 240 579 КМ², ВНУТРЕННИЕ ВОДЫ — 3230 КМ². ПО ДАННЫМ НА 1993 ГОД 10% СУШИ БЫЛИ ПОКРЫТЫ ЛЕСОМ, 46% ИСПОЛЬЗОВАЛИСЬ ПОД ПАСТБИЩА, А ЕЩЁ 25% ИСПОЛЬЗОВАЛОСЬ В ЗЕМЛЕДЕЛИИ. ЮЖНОЕ ПОБЕРЕЖЬЕ СОЕДИНЕНО С КОНТИНЕНТАЛЬНОЙ

Bering Stencil Light, Bold,
12/15,5 pt

GREAT BRITAIN, ALSO KNOWN AS BRITAIN, IS AN ISLAND IN THE NORTH ATLANTIC OFF THE NORTH-WEST COAST OF CONTINENTAL EUROPE. **WITH AN AREA OF 209,331 KM² (80,823 SQ MI),** IT IS THE LARGEST ISLAND IN EUROPE AND THE NINTH-LARGEST IN THE WORLD. IN 2011 THE ISLAND HAD A POPULATION OF ABOUT 61 MILLION PEOPLE, MAKING IT THE THIRD-MOST POPULOUS ISLAND IN THE WORLD, AFTER JAVA IN INDONESIA AND HONSHU IN JAPAN. IT ACCOUNTS FOR THE MAJORITY OF THE BRITISH ISLES ARCHIPELAGO, **ALONG WITH OVER 1,000 SMALLER SURROUNDING ISLANDS,** INCLUDING THE ISLAND OF IRELAND TO ITS WEST. THE ISLAND IS

ГОСУДАРСТВО РАСПОЛАГАЕТСЯ НА БРИТАНСКИХ ОСТРОВАХ (ОСТРОВ ВЕЛИКОБРИТАНИЯ, СЕВЕРО-ВОСТОЧНАЯ ЧАСТЬ ОСТРОВА ИРЛАНДИЯ, А ТАКЖЕ БОЛЬШОЕ КОЛИЧЕСТВО БОЛЕЕ МЕЛКИХ ОСТРОВОВ И АРХИПЕЛАГОВ. ОМЫВАЕТСЯ СЕВЕРНЫМ, ИРЛАНДСКИМ, КЕЛЬТСКИМ И ГЕБРИДСКИМ МОРЯМИ. **ПЛОЩАДЬ ВЕЛИКОБРИТАНИИ СОСТАВЛЯЕТ 243 809 КМ², ИЗ НИХ СУША — 240 579 КМ²,** ВНУТРЕННИЕ ВОДЫ — 3230 КМ². ПО ДАННЫМ НА 1993 ГОД 10% СУШИ БЫЛИ ПОКРЫТЫ ЛЕСОМ, 46% ИСПОЛЬЗОВАЛИСЬ ПОД ПАСТБИЩА, А ЕЩЁ 25% ИСПОЛЬЗОВАЛОСЬ В ЗЕМЛЕДЕЛИИ. КАЖДАЯ СТРАНА СОЕДИНЁННОГО КОРОЛЕВСТВА ИМЕЕТ СВОЮ СОБСТВЕННУЮ

Bering Stencil Narrow Thin, 6/8,5 pt

GREAT BRITAIN, ALSO KNOWN AS BRITAIN, IS AN ISLAND IN THE NORTH ATLANTIC OFF THE NORTH-WEST COAST OF CONTINENTAL EUROPE. WITH AN AREA OF 209,331 KM² (80,823 SQ MI), IT IS THE LARGEST ISLAND IN EUROPE AND THE NINTH-LARGEST IN THE WORLD. IN 2011 THE ISLAND HAD A POPULATION OF ABOUT 61 MILLION PEOPLE, MAKING IT THE THIRD-MOST POPULOUS ISLAND IN THE WORLD, AFTER JAVA IN INDONESIA AND HONSHU IN JAPAN. IT ACCOUNTS FOR THE MAJORITY OF THE BRITISH ISLES ARCHIPELAGO, ALONG WITH OVER 1,000 SMALLER SURROUNDING ISLANDS, INCLUDING THE ISLAND OF IRELAND TO ITS WEST. THE ISLAND IS PART OF THE UNITED KINGDOM OF GREAT BRITAIN AND NORTHERN IRELAND, CONSTITUTING MOST OF ITS TERRITORY: MOST OF ENGLAND, SCOTLAND, AND WALES ARE ON THE ISLAND, WITH THEIR RESPECTIVE CAPITAL CITIES, LONDON, EDINBURGH, AND CARDIFF. POLITICALLY, THE TERM GREAT BRITAIN USUALLY

ГОСУДАРСТВО РАСПОЛАГАЕТСЯ НА БРИТАНСКИХ ОСТРОВАХ (ОСТРОВ ВЕЛИКОБРИТАНИЯ, СЕВЕРО-ВОСТОЧНАЯ ЧАСТЬ ОСТРОВА ИРЛАНДИЯ, А ТАКЖЕ БОЛЬШОЕ КОЛИЧЕСТВО БОЛЕЕ МЕЛКИХ ОСТРОВОВ И АРХИПЕЛАГОВ, СРЕДИ КОТОРЫХ ГЕБРИДСКИЕ, ОРКНЕЙСКИЕ И ШЕТЛАНДСКИЕ ОСТРОВА, АНГЛСИ, АРРАН, УАЙТ) В АТЛАНТИЧЕСКОМ ОКЕАНЕ. ОМЫВАЕТСЯ СЕВЕРНЫМ, ИРЛАНДСКИМ, КЕЛЬТСКИМ И ГЕБРИДСКИМ МОРЯМИ. ЮГО-ВОСТОЧНОЕ ПОБЕРЕЖЬЕ РАСПОЛАГАЕТСЯ ВСЕГО В 35 КМ ОТ СЕВЕРНОГО ПОБЕРЕЖЬЯ ФРАНЦИИ, КОТОРЫЕ РАЗДЕЛЕНЫ ПРОЛИВОМ ЛА-МАНШ. ПЛОЩАДЬ ВЕЛИКОБРИТАНИИ СОСТАВЛЯЕТ 243 809 КМ², ИЗ НИХ СУША — 240 579 КМ², ВНУТРЕННИЕ ВОДЫ — 3230 КМ². ПО ДАННЫМ НА 1993 ГОД 10% СУШИ БЫЛИ ПОКРЫТЫ ЛЕСОМ, 46% ИСПОЛЬЗОВАЛИСЬ ПОД ПАСТБИЩА, А ЕЩЁ 25% ИСПОЛЬЗОВАЛОСЬ В ЗЕМЛЕДЕЛИИ. БЕРЕГОВАЯ ЛИНИЯ ИМЕЕТ 17 820 КМ ДЛИНЫ. ЮЖНОЕ ПОБЕРЕЖЬЕ СОЕДИНЕНО

Bering Stencil Narrow Thin, 8/10,5 pt

GREAT BRITAIN, ALSO KNOWN AS BRITAIN, IS AN ISLAND IN THE NORTH ATLANTIC OFF THE NORTH-WEST COAST OF CONTINENTAL EUROPE. WITH AN AREA OF 209,331 KM² (80,823 SQ MI), IT IS THE LARGEST ISLAND IN EUROPE AND THE NINTH-LARGEST IN THE WORLD. IN 2011 THE ISLAND HAD A POPULATION OF ABOUT 61 MILLION PEOPLE, MAKING IT THE THIRD-MOST POPULOUS ISLAND IN THE WORLD, AFTER JAVA IN INDONESIA AND HONSHU IN JAPAN. IT ACCOUNTS FOR THE MAJORITY OF THE BRITISH ISLES ARCHIPELAGO, ALONG WITH OVER 1,000 SMALLER SURROUNDING ISLANDS, INCLUDING THE ISLAND OF IRELAND TO ITS

ГОСУДАРСТВО РАСПОЛАГАЕТСЯ НА БРИТАНСКИХ ОСТРОВАХ (ОСТРОВ ВЕЛИКОБРИТАНИЯ, СЕВЕРО-ВОСТОЧНАЯ ЧАСТЬ ОСТРОВА ИРЛАНДИЯ, А ТАКЖЕ БОЛЬШОЕ КОЛИЧЕСТВО БОЛЕЕ МЕЛКИХ ОСТРОВОВ И АРХИПЕЛАГОВ, СРЕДИ КОТОРЫХ ГЕБРИДСКИЕ, ОРКНЕЙСКИЕ И ШЕТЛАНДСКИЕ ОСТРОВА, АНГЛСИ, АРРАН, УАЙТ) В АТЛАНТИЧЕСКОМ ОКЕАНЕ. ОМЫВАЕТСЯ СЕВЕРНЫМ, ИРЛАНДСКИМ, КЕЛЬТСКИМ И ГЕБРИДСКИМ МОРЯМИ. ЮГО-ВОСТОЧНОЕ ПОБЕРЕЖЬЕ РАСПОЛАГАЕТСЯ ВСЕГО В 35 КМ ОТ СЕВЕРНОГО ПОБЕРЕЖЬЯ ФРАНЦИИ, КОТОРЫЕ РАЗДЕЛЕНЫ ПРОЛИВОМ ЛА-МАНШ. ПЛОЩАДЬ ВЕЛИКОБРИТАНИИ СОСТАВЛЯЕТ 243 809 КМ²,

Bering Stencil Narrow Thin, 10/13,5 pt

GREAT BRITAIN, ALSO KNOWN AS BRITAIN, IS AN ISLAND IN THE NORTH ATLANTIC OFF THE NORTH-WEST COAST OF CONTINENTAL EUROPE. WITH AN AREA OF 209,331 KM² (80,823 SQ MI), IT IS THE LARGEST ISLAND IN EUROPE AND THE NINTH-LARGEST IN THE WORLD. IN 2011 THE ISLAND HAD A POPULATION OF ABOUT 61 MILLION PEOPLE, MAKING IT THE THIRD-MOST POPULOUS ISLAND IN THE WORLD, AFTER JAVA IN INDONESIA AND HONSHU IN JAPAN. IT ACCOUNTS FOR THE MAJORITY OF THE BRITISH ISLES ARCHIPELAGO, ALONG WITH OVER 1,000 SMALLER SURROUNDING ISLANDS, INCLUDING THE ISLAND OF IRELAND TO ITS WEST. THE ISLAND IS PART OF THE UNITED KINGDOM OF GREAT BRITAIN AND NORTHERN IRELAND, CONSTITUTING MOST OF ITS TERRITORY: MOST OF ENGLAND, SCOTLAND, AND WALES ARE ON THE ISLAND, WITH THEIR RESPECTIVE CAPITAL CITIES, LONDON, EDINBURGH, AND CARDIFF. POLITICALLY, THE TERM GREAT BRITAIN USUALLY EXTENDS TO INCLUDE SURROUNDING ISLANDS THAT FORM PART OF ENGLAND, SCOTLAND, AND WALES. THE ISLAND IS DOMINATED BY AN OCEANIC CLIMATE WITH QUITE NARROW

ГОСУДАРСТВО РАСПОЛАГАЕТСЯ НА БРИТАНСКИХ ОСТРОВАХ (ОСТРОВ ВЕЛИКОБРИТАНИЯ, СЕВЕРО-ВОСТОЧНАЯ ЧАСТЬ ОСТРОВА ИРЛАНДИЯ, А ТАКЖЕ БОЛЬШОЕ КОЛИЧЕСТВО БОЛЕЕ МЕЛКИХ ОСТРОВОВ И АРХИПЕЛАГОВ, СРЕДИ КОТОРЫХ ГЕБРИДСКИЕ, ОРКНЕЙСКИЕ И ШЕТЛАНДСКИЕ ОСТРОВА, АНГЛСИ, АРРАН, УАЙТ) В АТЛАНТИЧЕСКОМ ОКЕАНЕ. ОМЫВАЕТСЯ СЕВЕРНЫМ, ИРЛАНДСКИМ, КЕЛЬТСКИМ И ГЕБРИДСКИМ МОРЯМИ. ЮГО-ВОСТОЧНОЕ ПОБЕРЕЖЬЕ РАСПОЛАГАЕТСЯ ВСЕГО В 35 КМ ОТ СЕВЕРНОГО ПОБЕРЕЖЬЯ ФРАНЦИИ, КОТОРЫЕ РАЗДЕЛЕНЫ ПРОЛИВОМ ЛА-МАНШ. ПЛОЩАДЬ ВЕЛИКОБРИТАНИИ СОСТАВЛЯЕТ 243 809 КМ², ИЗ НИХ СУША — 240 579 КМ², ВНУТРЕННИЕ ВОДЫ — 3230 КМ². ПО ДАННЫМ НА 1993 ГОД 10% СУШИ БЫЛИ ПОКРЫТЫ ЛЕСОМ, 46% ИСПОЛЬЗОВАЛИСЬ ПОД ПАСТБИЩА, А ЕЩЁ 25% ИСПОЛЬЗОВАЛОСЬ В ЗЕМЛЕДЕЛИИ. ЮЖНОЕ ПОБЕРЕЖЬЕ СОЕДИНЕНО С КОНТИНЕНТАЛЬНОЙ ЕВРОПОЙ ЧЕРЕЗ ЕВРОТОННЕЛЬ ДЛИНОЙ 50 КМ (ИЗ КОТОРЫХ 38 КМ ПОД ВОДОЙ). ЭТО САМЫЙ ДЛИННЫЙ ПОДВОДНЫЙ ТОННЕЛЬ В МИРЕ. КАЖДАЯ СТРАНА СОЕДИНЁННОГО КОРОЛЕВСТВА ИМЕЕТ СВОЮ СОБСТВЕННУЮ СИСТЕМУ АДМИНИСТРАТИВНОГО И ГЕОГРАФИЧЕСКОГО

Bering Stencil Narrow Thin, 12/15,5 pt

GREAT BRITAIN, ALSO KNOWN AS BRITAIN, IS AN ISLAND IN THE NORTH ATLANTIC OFF THE NORTH-WEST COAST OF CONTINENTAL EUROPE. WITH AN AREA OF 209,331 KM² (80,823 SQ MI), IT IS THE LARGEST ISLAND IN EUROPE AND THE NINTH-LARGEST IN THE WORLD. IN 2011 THE ISLAND HAD A POPULATION OF ABOUT 61 MILLION PEOPLE, MAKING IT THE THIRD-MOST POPULOUS ISLAND IN THE WORLD, AFTER JAVA IN INDONESIA AND HONSHU IN JAPAN. IT ACCOUNTS FOR THE MAJORITY OF THE BRITISH ISLES ARCHIPELAGO, ALONG WITH OVER 1,000 SMALLER SURROUNDING ISLANDS, INCLUDING THE ISLAND OF IRELAND TO ITS WEST. THE ISLAND IS PART OF THE UNITED KINGDOM OF GREAT BRITAIN AND NORTHERN IRELAND, CONSTITUTING MOST OF ITS TERRITORY. THE ROMANS CONQUERED MOST OF THE ISLAND (UP TO HADRIAN'S WALL, IN NORTHERN ENGLAND)

ГОСУДАРСТВО РАСПОЛАГАЕТСЯ НА БРИТАНСКИХ ОСТРОВАХ (ОСТРОВ ВЕЛИКОБРИТАНИЯ, СЕВЕРО-ВОСТОЧНАЯ ЧАСТЬ ОСТРОВА ИРЛАНДИЯ, А ТАКЖЕ БОЛЬШОЕ КОЛИЧЕСТВО БОЛЕЕ МЕЛКИХ ОСТРОВОВ И АРХИПЕЛАГОВ. ОМЫВАЕТСЯ СЕВЕРНЫМ, ИРЛАНДСКИМ, КЕЛЬТСКИМ И ГЕБРИДСКИМ МОРЯМИ. ПЛОЩАДЬ ВЕЛИКОБРИТАНИИ СОСТАВЛЯЕТ 243 809 КМ², ИЗ НИХ СУША — 240 579 КМ², ВНУТРЕННИЕ ВОДЫ — 3230 КМ². ПО ДАННЫМ НА 1993 ГОД 10% СУШИ БЫЛИ ПОКРЫТЫ ЛЕСОМ, 46% ИСПОЛЬЗОВАЛИСЬ ПОД ПАСТБИЩА, А ЕЩЁ 25% ИСПОЛЬЗОВАЛОСЬ В ЗЕМЛЕДЕЛИИ. КАЖДАЯ СТРАНА СОЕДИНЁННОГО КОРОЛЕВСТВА ИМЕЕТ СВОЮ СОБСТВЕННУЮ СИСТЕМУ АДМИНИСТРАТИВНОГО И ГЕОГРАФИЧЕСКОГО ДЕЛЕНИЯ, КОТОРОЕ ЧАСТО ИСХОДИТ ЕЩЁ СО ВРЕМЁН ДО ПОЯВЛЕНИЯ ГОСУДАРСТВА ВЕЛИКОБРИТАНИЯ. СООТВЕТСТВЕННО «НЕ СУЩЕСТВУЕТ

Bering Stencil Narrow Light, 6/8,5 pt

GREAT BRITAIN, ALSO KNOWN AS BRITAIN, IS AN ISLAND IN THE NORTH ATLANTIC OFF THE NORTH-WEST COAST OF CONTIMENTAL EUROPE. WITH AN AREA OF 209,331 KM² (80,823 SQ MI), IT IS THE LARGEST ISLAND IN EUROPE AND THE NINTH-LARGEST IN THE WORLD. IN 2011 THE ISLAND HAD A POPULATION OF ABOUT 61 MILLION PEOPLE, MAKING IT THE THIRD-MOST POPULOUS ISLAND IN THE WORLD, AFTER JAVA IN INDOMESIA AND HONSHU IN JAPAN. IT ACCOUNTS FOR THE MAJORITY OF THE BRITISH ISLES ARCHIPELAGO, ALONG WITH OVER 1,000 SMALLER SURROUNDING ISLANDS, INCLUDING THE ISLAND OF IRELAND TO ITS WEST. THE ISLAND IS PART OF THE UNITED KINGDOM OF GREAT BRITAIN AND NORTHERN IRELAND, CONSTITUTING MOST OF ITS TERRITORY: MOST OF ENGLAND, SCOTLAND, AND WALES ARE ON THE ISLAND, WITH THEIR RESPECTIVE CAPITAL

ГОСУДАРСТВО РАСПОЛАГАЕТСЯ НА БРИТАНСКИХ ОСТРОВАХ (ОСТРОВ ВЕЛИКОБРИТАНИЯ, СЕВЕРО-ВОСТОЧНАЯ ЧАСТЬ ОСТРОВА ИРЛАНДИЯ, А ТАКЖЕ БОЛЬШОЕ КОЛИЧЕСТВО БОЛЕЕ МЕЛКИХ ОСТРОВОВ И АРХИПЕЛАГОВ, СРЕДИ КОТОРЫХ ГЕБРИДСКИЕ, ОРКНЕЙСКИЕ И ШЕТЛАНДСКИЕ ОСТРОВА, АНГЛСИ, АРРАН, УАЙТ) В АТЛАНТИЧЕСКОМ ОКЕАНЕ. ОМЫВАЕТСЯ СЕВЕРНЫМ, ИРЛАНДСКИМ, КЕЛЬТСКИМ И ГЕБРИДСКИМ МОРЯМИ. ЮГО-ВОСТОЧНОЕ ПОБЕРЕЖЬЕ РАСПОЛАГАЕТСЯ ВСЕГО В 35 КМ ОТ СЕВЕРНОГО ПОБЕРЕЖЬЯ ФРАНЦИИ, КОТОРЫЕ РАЗДЕЛЕНЫ ПРОЛИВОМ ЛА-МАНШ. ПЛОЩАДЬ ВЕЛИКОБРИТАНИИ СОСТАВЛЯЕТ 243 809 КМ², ИЗ НИХ СУША — 240 579 КМ², ВНУТРЕННИЕ ВОДЫ — 3230 КМ². ПО ДАННЫМ НА 1993 ГОД 10% СУШИ БЫЛИ ПОКРЫТЫ ЛЕСОМ, 46% ИСПОЛЬЗОВАЛИСЬ ПОД ПАСТБИЩА, А ЕЩЁ 25% ИСПОЛЬЗОВАЛОСЬ

Bering Stencil Narrow Light, 8/10,5 pt

GREAT BRITAIN, ALSO KNOWN AS BRITAIN, IS AN ISLAND IN THE NORTH ATLANTIC OFF THE NORTH-WEST COAST OF CONTIMENTAL EUROPE. WITH AN AREA OF 209,331 KM² (80,823 SQ MI), IT IS THE LARGEST ISLAND IN EUROPE AND THE NINTH-LARGEST IN THE WORLD. IN 2011 THE ISLAND HAD A POPULATION OF ABOUT 61 MILLION PEOPLE, MAKING IT THE THIRD-MOST POPULOUS ISLAND IN THE WORLD, AFTER JAVA IN INDOMESIA AND HONSHU IN JAPAN. IT ACCOUNTS FOR THE MAJORITY OF THE BRITISH ISLES ARCHIPELAGO, ALONG WITH OVER 1,000 SMALLER SURROUNDING

ГОСУДАРСТВО РАСПОЛАГАЕТСЯ НА БРИТАНСКИХ ОСТРОВАХ (ОСТРОВ ВЕЛИКОБРИТАНИЯ, СЕВЕРО-ВОСТОЧНАЯ ЧАСТЬ ОСТРОВА ИРЛАНДИЯ, А ТАКЖЕ БОЛЬШОЕ КОЛИЧЕСТВО БОЛЕЕ МЕЛКИХ ОСТРОВОВ И АРХИПЕЛАГОВ, СРЕДИ КОТОРЫХ ГЕБРИДСКИЕ, ОРКНЕЙСКИЕ И ШЕТЛАНДСКИЕ ОСТРОВА, АНГЛСИ, АРРАН, УАЙТ) В АТЛАНТИЧЕСКОМ ОКЕАНЕ. ОМЫВАЕТСЯ СЕВЕРНЫМ, ИРЛАНДСКИМ, КЕЛЬТСКИМ И ГЕБРИДСКИМ МОРЯМИ. ЮГО-ВОСТОЧНОЕ ПОБЕРЕЖЬЕ РАСПОЛАГАЕТСЯ ВСЕГО В 35 КМ ОТ СЕВЕРНОГО ПОБЕРЕЖЬЯ ФРАНЦИИ, КОТОРЫЕ РАЗДЕЛЕНЫ

Bering Stencil Narrow Light, 10/13,5 pt

GREAT BRITAIN, ALSO KNOWN AS BRITAIN, IS AN ISLAND IN THE NORTH ATLANTIC OFF THE NORTH-WEST COAST OF CONTINENTAL EUROPE. WITH AN AREA OF 209,331 KM² (80,823 SQ MI), IT IS THE LARGEST ISLAND IN EUROPE AND THE NINTH-LARGEST IN THE WORLD. IN 2011 THE ISLAND HAD A POPULATION OF ABOUT 61 MILLION PEOPLE, MAKING IT THE THIRD-MOST POPULOUS ISLAND IN THE WORLD, AFTER JAVA IN INDONESIA AND HONSHU IN JAPAN. IT ACCOUNTS FOR THE MAJORITY OF THE BRITISH ISLES ARCHIPELAGO, ALONG WITH OVER 1,000 SMALLER SURROUNDING ISLANDS, INCLUDING THE ISLAND OF IRELAND TO ITS WEST. THE ISLAND IS PART OF THE UNITED KINGDOM OF GREAT BRITAIN AND NORTHERN IRELAND, CONSTITUTING MOST OF ITS TERRITORY: MOST OF ENGLAND, SCOTLAND, AND WALES ARE ON THE ISLAND, WITH THEIR RESPECTIVE CAPITAL CITIES, LONDON, EDINBURGH, AND CARDIFF. POLITICALLY, THE TERM GREAT BRITAIN USUALLY EXTENDS TO INCLUDE SURROUNDING ISLANDS THAT FORM PART OF ENGLAND, SCOTLAND,

ГОСУДАРСТВО РАСПОЛАГАЕТСЯ НА БРИТАНСКИХ ОСТРОВАХ (ОСТРОВ ВЕЛИКОБРИТАНИЯ, СЕВЕРО-ВОСТОЧНАЯ ЧАСТЬ ОСТРОВА ИРЛАНДИЯ, А ТАКЖЕ БОЛЬШОЕ КОЛИЧЕСТВО БОЛЕЕ МЕЛКИХ ОСТРОВОВ И АРХИПЕЛАГОВ, СРЕДИ КОТОРЫХ ГЕБРИДСКИЕ, ОРКНЕЙСКИЕ И ШЕТЛАНДСКИЕ ОСТРОВА, АНГЛСИ, АРРАН, УАЙТ) В АТЛАНТИЧЕСКОМ ОКЕАНЕ. ОМЫВАЕТСЯ СЕВЕРНЫМ, ИРЛАНДСКИМ, КЕЛЬТСКИМ И ГЕБРИДСКИМ МОРЯМИ. ЮГО-ВОСТОЧНОЕ ПОБЕРЕЖЬЕ РАСПОЛАГАЕТСЯ ВСЕГО В 35 КМ ОТ СЕВЕРНОГО ПОБЕРЕЖЬЯ ФРАНЦИИ, КОТОРЫЕ РАЗДЕЛЕНЫ ПРОЛИВОМ ЛА-МАНШ. ПЛОЩАДЬ ВЕЛИКОБРИТАНИИ СОСТАВЛЯЕТ 243 809 КМ², ИЗ НИХ СУША — 240 579 КМ², ВНУТРЕННИЕ ВОДЫ — 3230 КМ². ПО ДАННЫМ НА 1993 ГОД 10% СУШИ БЫЛИ ПОКРЫТЫ ЛЕСОМ, 46% ИСПОЛЬЗОВАЛИСЬ ПОД ПАСТБИЩА, А ЕЩЁ 25% ИСПОЛЬЗОВАЛОСЬ В ЗЕМЛЕДЕЛИИ. ЮЖНОЕ ПОБЕРЕЖЬЕ СОЕДИНЕНО С КОНТИНЕНТАЛЬНОЙ ЕВРОПОЙ ЧЕРЕЗ ЕВРОТОННЕЛЬ ДЛИНОЙ 50 КМ (ИЗ КОТОРЫХ 38 КМ ПОД ВОДОЙ). ЭТО САМЫЙ ДЛИННЫЙ ПОДВОДНЫЙ ТОННЕЛЬ В МИРЕ.

Bering Stencil Narrow Light, 12/15,5 pt

GREAT BRITAIN, ALSO KNOWN AS BRITAIN, IS AN ISLAND IN THE NORTH ATLANTIC OFF THE NORTH-WEST COAST OF CONTINENTAL EUROPE. WITH AN AREA OF 209,331 KM² (80,823 SQ MI), IT IS THE LARGEST ISLAND IN EUROPE AND THE NINTH-LARGEST IN THE WORLD. IN 2011 THE ISLAND HAD A POPULATION OF ABOUT 61 MILLION PEOPLE, MAKING IT THE THIRD-MOST POPULOUS ISLAND IN THE WORLD, AFTER JAVA IN INDOMESIA AND HONSHU IN JAPAN. IT ACCOUNTS FOR THE MAJORITY OF THE BRITISH ISLES ARCHIPELAGO, ALONG WITH OVER 1,000 SMALLER SURROUNDING ISLANDS, INCLUDING THE ISLAND OF IRELAND TO ITS WEST. THE ISLAND IS PART OF THE UNITED KINGDOM OF GREAT BRITAIN AND NORTHERN IRELAND, CONSTITUTING MOST OF ITS TERRITORY. THE ROMANS

ГОСУДАРСТВО РАСПОЛАГАЕТСЯ НА БРИТАНСКИХ ОСТРОВАХ (ОСТРОВ ВЕЛИКОБРИТАНИЯ, СЕВЕРО-ВОСТОЧНАЯ ЧАСТЬ ОСТРОВА ИРЛАНДИЯ, А ТАКЖЕ БОЛЬШОЕ КОЛИЧЕСТВО БОЛЕЕ МЕЛКИХ ОСТРОВОВ И АРХИПЕЛАГОВ. ОМЫВАЕТСЯ СЕВЕРНЫМ, ИРЛАНДСКИМ, КЕЛЬТСКИМ И ГЕБРИДСКИМ МОРЯМИ. ПЛОЩАДЬ ВЕЛИКОБРИТАНИИ СОСТАВЛЯЕТ 243 809 КМ², ИЗ НИХ СУША — 240 579 КМ², ВНУТРЕННИЕ ВОДЫ — 3230 КМ². ПО ДАННЫМ НА 1993 ГОД 10% СУШИ БЫЛИ ПОКРЫТЫ ЛЕСОМ, 46% ИСПОЛЬЗОВАЛИСЬ ПОД ПАСТБИЩА, А ЕЩЁ 25% ИСПОЛЬЗОВАЛОСЬ В ЗЕМЛЕДЕЛИИ. КАЖДАЯ СТРАНА СОЕДИНЁННОГО КОРОЛЕВСТВА ИМЕЕТ СВОЮ СОБСТВЕННУЮ СИСТЕМУ АДМИНИСТРАТИВНОГО И ГЕОГРАФИЧЕСКОГО ДЕЛЕНИЯ, КОТОРОЕ ЧАСТО ИСХОДИТ ЕЩЁ СО ВРЕМЁН ДО ПОЯВЛЕНИЯ

Bering Stencil Narrow Regular, 6/8,5 pt

GREAT BRITAIN, ALSO KNOWN AS BRITAIN, IS AN ISLAND IN THE NORTH ATLANTIC OFF THE NORTH-WEST COAST OF CONTINENTAL EUROPE. WITH AN AREA OF 209,331 KM² (80,823 SQ MI), IT IS THE LARGEST ISLAND IN EUROPE AND THE NINTH-LARGEST IN THE WORLD. IN 2011 THE ISLAND HAD A POPULATION OF ABOUT 61 MILLION PEOPLE, MAKING IT THE THIRD-MOST POPULOUS ISLAND IN THE WORLD, AFTER JAVA IN INDONESIA AND HONSHU IN JAPAN. IT ACCOUNTS FOR THE MAJORITY OF THE BRITISH ISLES ARCHIPELAGO, ALONG WITH OVER 1,000 SMALLER SURROUNDING ISLANDS, INCLUDING THE ISLAND OF IRELAND TO ITS WEST. THE ISLAND IS PART OF THE UNITED KINGDOM OF GREAT BRITAIN AND NORTHERN IRELAND, CONSTITUTING MOST OF ITS TERRITORY: MOST OF ENGLAND, SCOT-

ГОСУДАРСТВО РАСПОЛАГАЕТСЯ НА БРИТАНСКИХ ОСТРОВАХ (ОСТРОВ ВЕЛИКОБРИТАНИЯ, СЕВЕРО-ВОСТОЧНАЯ ЧАСТЬ ОСТРОВА ИРЛАНДИЯ, А ТАКЖЕ БОЛЬШОЕ КОЛИЧЕСТВО БОЛЕЕ МЕЛКИХ ОСТРОВОВ И АРХИПЕЛАГОВ, СРЕДИ КОТОРЫХ ГЕБРИДСКИЕ, ОРКНЕЙСКИЕ И ШЕТЛАНДСКИЕ ОСТРОВА, АНГЛСИ, АРРАН, УАЙТ) В АТЛАНТИЧЕСКОМ ОКЕАНЕ. ОМЫВАЕТСЯ СЕВЕРНЫМ, ИРЛАНДСКИМ, КЕЛЬТСКИМ И ГЕБРИДСКИМ МОРЯМИ. ЮГО-ВОСТОЧНОЕ ПОБЕРЕЖЬЕ РАСПОЛАГАЕТСЯ ВСЕГО В 35 КМ ОТ СЕВЕРНОГО ПОБЕРЕЖЬЯ ФРАНЦИИ, КОТОРЫЕ РАЗДЕЛЕНЫ ПРОЛИВОМ ЛА-МАНШ. ПЛОЩАДЬ ВЕЛИКОБРИТАНИИ СОСТАВЛЯЕТ 243 809 КМ², ИЗ НИХ СУША — 240 579 КМ², ВНУТРЕННИЕ ВОДЫ — 3230 КМ². ПО ДАННЫМ НА 1993 ГОД 10% СУШИ БЫЛИ ПОКРЫТЫ ЛЕСОМ,

Bering Stencil Narrow Regular, 8/10,5 pt

GREAT BRITAIN, ALSO KNOWN AS BRITAIN, IS AN ISLAND IN THE NORTH ATLANTIC OFF THE NORTH-WEST COAST OF CONTINENTAL EUROPE. WITH AN AREA OF 209,331 KM² (80,823 SQ MI), IT IS THE LARGEST ISLAND IN EUROPE AND THE NINTH-LARGEST IN THE WORLD. IN 2011 THE ISLAND HAD A POPULATION OF ABOUT 61 MILLION PEOPLE, MAKING IT THE THIRD-MOST POPULOUS ISLAND IN THE WORLD, AFTER JAVA IN INDONESIA AND HONSHU IN JAPAN. IT ACCOUNTS FOR THE MAJORITY OF THE BRITISH ISLES

ГОСУДАРСТВО РАСПОЛАГАЕТСЯ НА БРИТАНСКИХ ОСТРОВАХ (ОСТРОВ ВЕЛИКОБРИТАНИЯ, СЕВЕРО-ВОСТОЧНАЯ ЧАСТЬ ОСТРОВА ИРЛАНДИЯ, А ТАКЖЕ БОЛЬШОЕ КОЛИЧЕСТВО БОЛЕЕ МЕЛКИХ ОСТРОВОВ И АРХИПЕЛАГОВ, СРЕДИ КОТОРЫХ ГЕБРИДСКИЕ, ОРКНЕЙСКИЕ И ШЕТЛАНДСКИЕ ОСТРОВА, АНГЛСИ, АРРАН, УАЙТ) В АТЛАНТИЧЕСКОМ ОКЕАНЕ. ОМЫВАЕТСЯ СЕВЕРНЫМ, ИРЛАНДСКИМ, КЕЛЬТСКИМ И ГЕБРИДСКИМ МОРЯМИ. ЮГО-ВОСТОЧНОЕ ПОБЕРЕЖЬЕ РАСПОЛАГАЕТСЯ ВСЕГО В 35 КМ ОТ СЕВЕРНОГО

Bering Stencil Narrow Regular, 10/13,5 pt

GREAT BRITAIN, ALSO KNOWN AS BRITAIN, IS AN ISLAND IN THE NORTH ATLANTIC OFF THE NORTH-WEST COAST OF CONTINENTAL EUROPE. WITH AN AREA OF 209,331 KM² (80,823 SQ MI), IT IS THE LARGEST ISLAND IN EUROPE AND THE NINTH-LARGEST IN THE WORLD. IN 2011 THE ISLAND HAD A POPULATION OF ABOUT 61 MILLION PEOPLE, MAKING IT THE THIRD-MOST POPULOUS ISLAND IN THE WORLD, AFTER JAVA IN INDONESIA AND HONSHU IN JAPAN. IT ACCOUNTS FOR THE MAJORITY OF THE BRITISH ISLES ARCHIPELAGO, ALONG WITH OVER 1,000 SMALLER SURROUNDING ISLANDS, INCLUDING THE ISLAND OF IRELAND TO ITS WEST. THE ISLAND IS PART OF THE UNITED KINGDOM OF GREAT BRITAIN AND NORTHERN IRELAND, CONSTITUTING MOST OF ITS TERRITORY: MOST OF ENGLAND, SCOTLAND, AND WALES ARE ON THE ISLAND, WITH THEIR RESPECTIVE CAPITAL CITIES, LONDON, EDINBURGH, AND CARDIFF. POLITICALLY, THE TERM GREAT BRITAIN USUALLY

ГОСУДАРСТВО РАСПОЛАГАЕТСЯ НА БРИТАНСКИХ ОСТРОВАХ (ОСТРОВ ВЕЛИКОБРИТАНИЯ, СЕВЕРО-ВОСТОЧНАЯ ЧАСТЬ ОСТРОВА ИРЛАНДИЯ, А ТАКЖЕ БОЛЬШОЕ КОЛИЧЕСТВО БОЛЕЕ МЕЛКИХ ОСТРОВОВ И АРХИПЕЛАГОВ, СРЕДИ КОТОРЫХ ГЕБРИДСКИЕ, ОРКНЕЙСКИЕ И ШЕТЛАНДСКИЕ ОСТРОВА, АНГЛСИ, АРРАН, УАЙТ) В АТЛАНТИЧЕСКОМ ОКЕАНЕ. ОМЫВАЕТСЯ СЕВЕРНЫМ, ИРЛАНДСКИМ, КЕЛЬТСКИМ И ГЕБРИДСКИМ МОРЯМИ. ЮГО-ВОСТОЧНОЕ ПОБЕРЕЖЬЕ РАСПОЛАГАЕТСЯ ВСЕГО В 35 КМ ОТ СЕВЕРНОГО ПОБЕРЕЖЬЯ ФРАНЦИИ, КОТОРЫЕ РАЗДЕЛЕНЫ ПРОЛИВОМ ЛА-МАНШ. ПЛОЩАДЬ ВЕЛИКОБРИТАНИИ СОСТАВЛЯЕТ 243 809 КМ², ИЗ НИХ СУША — 240 579 КМ², ВНУТРЕННИЕ ВОДЫ — 3230 КМ². ПО ДАННЫМ НА 1993 ГОД 10% СУШИ БЫЛИ ПОКРЫТЫ ЛЕСОМ, 46% ИСПОЛЬЗОВАЛИСЬ ПОД ПАСТБИЩА, А ЕЩЁ 25% ИСПОЛЬЗОВАЛОСЬ В ЗЕМЛЕДЕЛИИ. ЮЖНОЕ ПОБЕРЕЖЬЕ СОЕДИНЕНО С КОНТИНЕНТАЛЬНОЙ ЕВРОПОЙ ЧЕРЕЗ ЕВРОТОННЕЛЬ ДЛИНОЙ 50 КМ (ИЗ КОТОРЫХ

Bering Stencil Narrow Regular, 12/15,5 pt

GREAT BRITAIN, ALSO KNOWN AS BRITAIN, IS AN ISLAND IN THE NORTH ATLANTIC OFF THE NORTH-WEST COAST OF CONTINENTAL EUROPE. WITH AN AREA OF 209,331 KM² (80,823 SQ MI), IT IS THE LARGEST ISLAND IN EUROPE AND THE NINTH-LARGEST IN THE WORLD. IN 2011 THE ISLAND HAD A POPULATION OF ABOUT 61 MILLION PEOPLE, MAKING IT THE THIRD-MOST POPULOUS ISLAND IN THE WORLD, AFTER JAVA IN INDONESIA AND HONSHU IN JAPAN. IT ACCOUNTS FOR THE MAJORITY OF THE BRITISH ISLES ARCHIPELAGO, ALONG WITH OVER 1,000 SMALLER SURROUNDING ISLANDS, INCLUDING THE ISLAND OF IRELAND TO ITS WEST. THE ISLAND IS PART OF THE UNITED KINGDOM OF GREAT BRITAIN AND

ГОСУДАРСТВО РАСПОЛАГАЕТСЯ НА БРИТАНСКИХ ОСТРОВАХ (ОСТРОВ ВЕЛИКОБРИТАНИЯ, СЕВЕРО-ВОСТОЧНАЯ ЧАСТЬ ОСТРОВА ИРЛАНДИЯ, А ТАКЖЕ БОЛЬШОЕ КОЛИЧЕСТВО БОЛЕЕ МЕЛКИХ ОСТРОВОВ И АРХИПЕЛАГОВ. ОМЫВАЕТСЯ СЕВЕРНЫМ, ИРЛАНДСКИМ, КЕЛЬТСКИМ И ГЕБРИДСКИМ МОРЯМИ. ПЛОЩАДЬ ВЕЛИКОБРИТАНИИ СОСТАВЛЯЕТ 243 809 КМ², ИЗ НИХ СУША — 240 579 КМ², ВНУТРЕННИЕ ВОДЫ — 3230 КМ². ПО ДАННЫМ НА 1993 ГОД 10% СУШИ БЫЛИ ПОКРЫТЫ ЛЕСОМ, 46% ИСПОЛЬЗОВАЛИСЬ ПОД ПАСТБИЩА, А ЕЩЁ 25% ИСПОЛЬЗОВАЛОСЬ В ЗЕМЛЕДЕЛИИ. КАЖДАЯ СТРАНА СОЕДИНЁННОГО КОРОЛЕВСТВА ИМЕЕТ СВОЮ СОБСТВЕННУЮ СИСТЕМУ АДМИНИСТРАТИВНОГО И ГЕОГРАФИЧЕСКОГО ДЕЛЕНИЯ, КО-

Bering Stencil Narrow Bold, 6/8,5 pt

GREAT BRITAIN, ALSO KNOWN AS BRITAIN, IS AN ISLAND IN THE NORTH ATLANTIC OFF THE NORTH-WEST COAST OF CONTINENTAL EUROPE. WITH AN AREA OF 209,331 KM² (80,823 SQ MI), IT IS THE LARGEST ISLAND IN EUROPE AND THE NINTH-LARGEST IN THE WORLD. IN 2011 THE ISLAND HAD A POPULATION OF ABOUT 61 MILLION PEOPLE, MAKING IT THE THIRD-MOST POPULOUS ISLAND IN THE WORLD, AFTER JAVA IN INDONESIA AND HONSHU IN JAPAN. IT ACCOUNTS FOR THE MAJORITY OF THE BRITISH ISLES ARCHIPELAGO, ALONG WITH OVER 1,000 SMALLER SURROUNDING ISLANDS, INCLUDING THE ISLAND OF IRELAND TO ITS WEST. THE ISLAND IS PART OF THE UNITED KINGDOM OF GREAT BRITAIN AND

ГОСУДАРСТВО РАСПОЛАГАЕТСЯ НА БРИТАНСКИХ ОСТРОВАХ (ОСТРОВ ВЕЛИКОБРИТАНИЯ, СЕВЕРО-ВОСТОЧНАЯ ЧАСТЬ ОСТРОВА ИРЛАНДИЯ, А ТАКЖЕ БОЛЬШОЕ КОЛИЧЕСТВО БОЛЕЕ МЕЛКИХ ОСТРОВОВ И АРХИПЕЛАГОВ, СРЕДИ КОТОРЫХ ГЕБРИДСКИЕ, ОРКНЕЙСКИЕ И ШЕТЛАНДСКИЕ ОСТРОВА, АНГЛСИ, АРРАН, УАЙТ) В АТЛАНТИЧЕСКОМ ОКЕАНЕ. ОМЫВАЕТСЯ СЕВЕРНЫМ, ИРЛАНДСКИМ, КЕЛЬТСКИМ И ГЕБРИДСКИМ МОРЯМИ. ЮГО-ВОСТОЧНОЕ ПОБЕРЕЖЬЕ РАСПОЛАГАЕТСЯ ВСЕГО В 35 КМ ОТ СЕВЕРНОГО ПОБЕРЕЖЬЯ ФРАНЦИИ, КОТОРЫЕ РАЗДЕЛЕНЫ ПРОЛИВОМ ЛА-МАНШ. ПЛОЩАДЬ ВЕЛИКОБРИТАНИИ СОСТАВЛЯЕТ 243 809 КМ², ИЗ НИХ СУША — 240 579 КМ², ВНУТРЕННИЕ ВОДЫ — 3230 КМ². ПО ДАННЫМ

Bering Stencil Narrow Bold, 8/10,5 pt

GREAT BRITAIN, ALSO KNOWN AS BRITAIN, IS AN ISLAND IN THE NORTH ATLANTIC OFF THE NORTH-WEST COAST OF CONTINENTAL EUROPE. WITH AN AREA OF 209,331 KM² (80,823 SQ MI), IT IS THE LARGEST ISLAND IN EUROPE AND THE NINTH-LARGEST IN THE WORLD. IN 2011 THE ISLAND HAD A POPULATION OF ABOUT 61 MILLION PEOPLE, MAKING IT THE THIRD-MOST POPULOUS ISLAND IN THE WORLD, AFTER JAVA IN INDONESIA AND HONSHU IN JAPAN. IT ACCOUNTS FOR THE

ГОСУДАРСТВО РАСПОЛАГАЕТСЯ НА БРИТАНСКИХ ОСТРОВАХ (ОСТРОВ ВЕЛИКОБРИТАНИЯ, СЕВЕРО-ВОСТОЧНАЯ ЧАСТЬ ОСТРОВА ИРЛАНДИЯ, А ТАКЖЕ БОЛЬШОЕ КОЛИЧЕСТВО БОЛЕЕ МЕЛКИХ ОСТРОВОВ И АРХИПЕЛАГОВ, СРЕДИ КОТОРЫХ ГЕБРИДСКИЕ, ОРКНЕЙСКИЕ И ШЕТЛАНДСКИЕ ОСТРОВА, АНГЛСИ, АРРАН, УАЙТ) В АТЛАНТИЧЕСКОМ ОКЕАНЕ. ОМЫВАЕТСЯ СЕВЕРНЫМ, ИРЛАНДСКИМ, КЕЛЬТСКИМ И ГЕБРИДСКИМ МОРЯМИ. ЮГО-ВОСТОЧНОЕ ПОБЕРЕЖЬЕ

Bering Stencil Narrow Bold, 10/13,5 pt

GREAT BRITAIN, ALSO KNOWN AS BRITAIN, IS AN ISLAND IN THE NORTH ATLANTIC OFF THE NORTH-WEST COAST OF CONTINENTAL EUROPE. WITH AN AREA OF 209,331 KM² (80,823 SQ MI), IT IS THE LARGEST ISLAND IN EUROPE AND THE NINTH-LARGEST IN THE WORLD. IN 2011 THE ISLAND HAD A POPULATION OF ABOUT 61 MILLION PEOPLE, MAKING IT THE THIRD-MOST POPULOUS ISLAND IN THE WORLD, AFTER JAVA IN INDONESIA AND HONSHU IN JAPAN. IT ACCOUNTS FOR THE MAJORITY OF THE BRITISH ISLES ARCHIPELAGO, ALONG WITH OVER 1,000 SMALLER SURROUNDING ISLANDS, INCLUDING THE ISLAND OF IRELAND TO ITS WEST. THE ISLAND IS PART OF THE UNITED KINGDOM OF GREAT BRITAIN AND NORTHERN IRELAND, CONSTITUTING MOST OF ITS TERRITORY: MOST OF ENGLAND, SCOTLAND, AND WALES ARE ON THE ISLAND, WITH THEIR RESPECTIVE CAPITAL CITIES,

ГОСУДАРСТВО РАСПОЛАГАЕТСЯ НА БРИТАНСКИХ ОСТРОВАХ (ОСТРОВ ВЕЛИКОБРИТАНИЯ, СЕВЕРО-ВОСТОЧНАЯ ЧАСТЬ ОСТРОВА ИРЛАНДИЯ, А ТАКЖЕ БОЛЬШОЕ КОЛИЧЕСТВО БОЛЕЕ МЕЛКИХ ОСТРОВОВ И АРХИПЕЛАГОВ, СРЕДИ КОТОРЫХ ГЕБРИДСКИЕ, ОРКНЕЙСКИЕ И ШЕТЛАНДСКИЕ ОСТРОВА, АНГЛСИ, АРРАН, УАЙТ) В АТЛАНТИЧЕСКОМ ОКЕАНЕ. ОМЫВАЕТСЯ СЕВЕРНЫМ, ИРЛАНДСКИМ, КЕЛЬТСКИМ И ГЕБРИДСКИМ МОРЯМИ. ЮГО-ВОСТОЧНОЕ ПОБЕРЕЖЬЕ РАСПОЛАГАЕТСЯ ВСЕГО В 35 КМ ОТ СЕВЕРНОГО ПОБЕРЕЖЬЯ ФРАНЦИИ, КОТОРЫЕ РАЗДЕЛЕНЫ ПРОЛИВОМ ЛА-МАНШ. ПЛОЩАДЬ ВЕЛИКОБРИТАНИИ СОСТАВЛЯЕТ 243 809 КМ², ИЗ НИХ СУША — 240 579 КМ², ВНУТРЕННИЕ ВОДЫ — 3230 КМ². ПО ДАННЫМ НА 1993 ГОД 10% СУШИ БЫЛИ ПОКРЫТЫ ЛЕСОМ, 46% ИСПОЛЬЗОВАЛИСЬ ПОД ПАСТБИЩА, А ЕЩЁ 25% ИСПОЛЬЗОВАЛОСЬ В ЗЕМЛЕДЕЛИИ. ЮЖНОЕ ПОБЕРЕЖЬЕ СОЕДИНЕНО

Bering Stencil Narrow Bold, 12/15,5 pt

GREAT BRITAIN, ALSO KNOWN AS BRITAIN, IS AN ISLAND IN THE NORTH ATLANTIC OFF THE NORTH-WEST COAST OF CONTINENTAL EUROPE. WITH AN AREA OF 209,331 KM² (80,823 SQ MI), IT IS THE LARGEST ISLAND IN EUROPE AND THE NINTH-LARGEST IN THE WORLD. IN 2011 THE ISLAND HAD A POPULATION OF ABOUT 61 MILLION PEOPLE, MAKING IT THE THIRD-MOST POPULOUS ISLAND IN THE WORLD, AFTER JAVA IN INDONESIA AND HONSHU IN JAPAN. IT ACCOUNTS FOR THE MAJORITY OF THE BRITISH ISLES ARCHIPELAGO, ALONG WITH OVER 1,000 SMALLER SURROUNDING ISLANDS, INCLUDING THE ISLAND OF IRELAND TO ITS WEST. THE ISLAND IS PART

ГОСУДАРСТВО РАСПОЛАГАЕТСЯ НА БРИТАНСКИХ ОСТРОВАХ (ОСТРОВ ВЕЛИКОБРИТАНИЯ, СЕВЕРО-ВОСТОЧНАЯ ЧАСТЬ ОСТРОВА ИРЛАНДИЯ, А ТАКЖЕ БОЛЬШОЕ КОЛИЧЕСТВО БОЛЕЕ МЕЛКИХ ОСТРОВОВ И АРХИПЕЛАГОВ. ОМЫВАЕТСЯ СЕВЕРНЫМ, ИРЛАНДСКИМ, КЕЛЬТСКИМ И ГЕБРИДСКИМ МОРЯМИ. ПЛОЩАДЬ ВЕЛИКОБРИТАНИИ СОСТАВЛЯЕТ 243 809 КМ², ИЗ НИХ СУША — 240 579 КМ², ВНУТРЕННИЕ ВОДЫ — 3230 КМ². ПО ДАННЫМ НА 1993 ГОД 10% СУШИ БЫЛИ ПОКРЫТЫ ЛЕСОМ, 46% ИСПОЛЬЗОВАЛИСЬ ПОД ПАСТБИЩА, А ЕЩЁ 25% ИСПОЛЬЗОВАЛОСЬ В ЗЕМЛЕДЕЛИИ. КАЖДАЯ СТРАНА СОЕДИНЁННОГО КОРОЛЕВСТВА ИМЕЕТ СВОЮ СОБСТВЕННУЮ

Bering Stencil Narrow Light, Bold, 6/8,5 pt

GREAT BRITAIN, ALSO KNOWN AS BRITAIN, IS AN ISLAND IN THE NORTH ATLANTIC OFF THE NORTH-WEST COAST OF CONTIMENTAL EUROPE. WITH AN AREA OF 209,331 KM² (80,823 SQ MI), IT IS THE LARGEST ISLAND IN EUROPE AND THE NINTH-LARGEST IN THE WORLD. IN 2011 THE ISLAND HAD A POPULATION OF ABOUT 61 MILLION PEOPLE, MAKING IT THE THIRD-MOST POPULOUS ISLAND IN THE WORLD, AFTER JAVA IN INDOMESIA AND HONSHU IN JAPAN. **IT ACCOUNTS FOR THE MAJORITY OF THE BRITISH ISLES ARCHIPELAGO,** ALONG WITH OVER 1,000 SMALLER SURROUNDING ISLANDS, INCLUDING THE ISLAND OF IRELAND TO ITS WEST. THE ISLAND IS PART OF THE UNITED KINGDOM OF GREAT BRITAIN AND NORTHERN IRELAND, CONSTITUTING MOST OF ITS TERRITORY: MOST OF ENGLAND, SCOTLAND, AND WALES ARE ON THE ISLAND, WITH THEIR

ГОСУДАРСТВО РАСПОЛАГАЕТСЯ НА БРИТАНСКИХ ОСТРОВАХ (ОСТРОВ ВЕЛИКОБРИТАНИЯ, СЕВЕРО-ВОСТОЧНАЯ ЧАСТЬ ОСТРОВА ИРЛАНДИЯ, А ТАКЖЕ БОЛЬШОЕ КОЛИЧЕСТВО БОЛЕЕ МЕЛКИХ ОСТРОВОВ И АРХИПЕЛАГОВ, СРЕДИ КОТОРЫХ ГЕБРИДСКИЕ, ОРКНЕЙСКИЕ И ШЕТЛАНДСКИЕ ОСТРОВА, АНГЛСИ, АРРАН, УАЙТ) В АТЛАНТИЧЕСКОМ ОКЕАНЕ. **ОМЫВАЕТСЯ СЕВЕРНЫМ, ИРЛАНДСКИМ, КЕЛЬТСКИМ И ГЕБРИДСКИМ МОРЯМИ.** ЮГО-ВОСТОЧНОЕ ПОБЕРЕЖЬЕ РАСПОЛАГАЕТСЯ ВСЕГО В 35 КМ ОТ СЕВЕРНОГО ПОБЕРЕЖЬЯ ФРАНЦИИ, КОТОРЫЕ РАЗДЕЛЕНЫ ПРОЛИВОМ ЛА-МАНШ. ПЛОЩАДЬ ВЕЛИКОБРИТАНИИ СОСТАВЛЯЕТ 243 809 КМ², ИЗ НИХ СУША — 240 579 КМ², ВНУТРЕННИЕ ВОДЫ — 3230 КМ². ПО ДАННЫМ НА 1993 ГОД 10% СУШИ БЫЛИ ПОКРЫТЫ ЛЕСОМ, 46% ИСПОЛЬЗОВАЛИСЬ ПОД ПАСТБИЩА, А ЕЩЁ 25%

Bering Stencil Narrow Light, Bold, 8/10,5 pt

GREAT BRITAIN, ALSO KNOWN AS BRITAIN, IS AN ISLAND IN THE NORTH ATLANTIC OFF THE NORTH-WEST COAST OF CONTIMENTAL EUROPE. WITH AN AREA OF 209,331 KM² (80,823 SQ MI), IT IS THE LARGEST ISLAND IN EUROPE AND THE NINTH-LARGEST IN THE WORLD. **IN 2011 THE ISLAND HAD A POPULATION OF ABOUT 61 MILLION PEOPLE,** MAKING IT THE THIRD-MOST POPULOUS ISLAND IN THE WORLD, AFTER JAVA IN INDONESIA AND HONSHU IN JAPAN. IT ACCOUNTS FOR THE MAJORITY OF THE BRITISH ISLES ARCHIPELAGO, ALONG WITH OVER 1,000 SMALLER

ГОСУДАРСТВО РАСПОЛАГАЕТСЯ НА БРИТАНСКИХ ОСТРОВАХ (ОСТРОВ ВЕЛИКОБРИТАНИЯ, СЕВЕРО-ВОСТОЧНАЯ ЧАСТЬ ОСТРОВА ИРЛАНДИЯ, А ТАКЖЕ БОЛЬШОЕ КОЛИЧЕСТВО БОЛЕЕ МЕЛКИХ ОСТРОВОВ И АРХИПЕ-ЛАГОВ, **СРЕДИ КОТОРЫХ ГЕБРИДСКИЕ, ОРКНЕЙСКИЕ И ШЕТ-ЛАНДСКИЕ ОСТРОВА, АНГЛСИ, АРРАН, УАЙТ)** В АТЛАНТИЧЕСКОМ ОКЕАНЕ. ОМЫВАЕТСЯ СЕВЕРНЫМ, ИРЛАНДСКИМ, КЕЛЬТСКИМ И ГЕБРИД-СКИМ МОРЯМИ. ЮГО-ВОСТОЧНОЕ ПОБЕРЕЖЬЕ РАСПОЛАГАЕТСЯ ВСЕГО В 35 КМ ОТ СЕВЕРНОГО ПОБЕРЕЖЬЯ ФРАНЦИИ, КОТОРЫЕ РАЗДЕЛЕНЫ

Bering Stencil Narrow Light, Bold, 10/13,5 pt

GREAT BRITAIN, ALSO KNOWN AS BRITAIN, IS AN ISLAND IN THE NORTH ATLANTIC OFF THE NORTH-WEST COAST OF CONTINENTAL EUROPE. WITH AN AREA OF 209,331 KM² (80,823 SQ MI), IT IS THE LARGEST ISLAND IN EUROPE AND THE NINTH-LARGEST IN THE WORLD. IN 2011 THE ISLAND HAD A POPULATION OF ABOUT 61 MILLION PEOPLE, MAKING IT THE THIRD-MOST POPULOUS ISLAND IN THE WORLD, AFTER JAVA IN INDONESIA AND HONSHU IN JAPAN. **IT ACCOUNTS FOR THE MAJORITY OF THE BRITISH ISLES ARCHIPELAGO, ALONG WITH OVER 1,000 SMALLER SURROUNDING ISLANDS, INCLUDING THE ISLAND OF IRELAND TO ITS WEST.** THE ISLAND IS PART OF THE UNITED KINGDOM OF GREAT BRITAIN AND NORTHERN IRELAND, CONSTITUTING MOST OF ITS TERRITORY: MOST OF ENGLAND, SCOTLAND, AND WALES ARE ON THE ISLAND, WITH THEIR RESPECTIVE CAPITAL CITIES, LONDON, EDINBURGH, AND CARDIFF. POLITICALLY, THE TERM GREAT BRITAIN USUALLY EXTENDS TO INCLUDE SURROUNDING

ГОСУДАРСТВО РАСПОЛАГАЕТСЯ НА БРИТАНСКИХ ОСТРОВАХ (ОСТРОВ ВЕЛИКОБРИТАНИЯ, СЕВЕРО-ВОСТОЧНАЯ ЧАСТЬ ОСТРОВА ИРЛАНДИЯ, А ТАКЖЕ БОЛЬШОЕ КОЛИЧЕСТВО БОЛЕЕ МЕЛКИХ ОСТРОВОВ И АРХИПЕЛАГОВ, СРЕДИ КОТОРЫХ ГЕБРИДСКИЕ, ОРКНЕЙСКИЕ И ШЕТЛАНДСКИЕ ОСТРОВА, АНГЛСИ, АРРАН, УАЙТ) В АТЛАНТИЧЕСКОМ ОКЕАНЕ. ОМЫВАЕТСЯ СЕВЕРНЫМ, ИРЛАНДСКИМ, КЕЛЬТСКИМ И ГЕБРИДСКИМ МОРЯМИ. **ЮГО-ВОСТОЧНОЕ ПОБЕРЕЖЬЕ РАСПОЛАГАЕТСЯ ВСЕГО В 35 КМ ОТ СЕВЕРНОГО ПОБЕРЕЖЬЯ ФРАНЦИИ, КОТОРЫЕ РАЗДЕЛЕНЫ ПРОЛИВОМ ЛА-МАНШ.** ПЛОЩАДЬ ВЕЛИКОБРИТАНИИ СОСТАВЛЯЕТ 243 809 КМ², ИЗ НИХ СУША — 240 579 КМ², ВНУТРЕННИЕ ВОДЫ — 3230 КМ². ПО ДАННЫМ НА 1993 ГОД 10% СУШИ БЫЛИ ПОКРЫТЫ ЛЕСОМ, 46% ИСПОЛЬЗОВАЛИСЬ ПОД ПАСТБИЩА, А ЕЩЁ 25% ИСПОЛЬЗОВАЛОСЬ В ЗЕМЛЕДЕЛИИ. ЮЖНОЕ ПОБЕРЕЖЬЕ СОЕДИНЕНО С КОНТИНЕНТАЛЬНОЙ ЕВРОПОЙ ЧЕРЕЗ ЕВРОТОННЕЛЬ ДЛИНОЙ 50 КМ (ИЗ КОТОРЫХ 38 КМ ПОД ВОДОЙ). ЭТО САМЫЙ ДЛИННЫЙ ПОДВОДНЫЙ ТОННЕЛЬ

Bering Stencil Narrow Light, Bold, 12/15,5 pt

GREAT BRITAIN, ALSO KNOWN AS BRITAIN, IS AN ISLAND IN THE NORTH ATLANTIC OFF THE NORTH-WEST COAST OF CONTINENTAL EUROPE. WITH AN AREA OF 209,331 KM² (80,823 SQ MI), IT IS THE LARGEST ISLAND IN EUROPE AND THE NINTH-LARGEST IN THE WORLD. **IN 2011 THE ISLAND HAD A POPULATION OF ABOUT 61 MILLION PEOPLE, MAKING IT THE THIRD-MOST POPULOUS ISLAND IN THE WORLD, AFTER JAVA IN INDONESIA AND HONSHU IN JAPAN.** IT ACCOUNTS FOR THE MAJORITY OF THE BRITISH ISLES ARCHIPELAGO, ALONG WITH OVER 1,000 SMALLER SURROUNDING ISLANDS, INCLUDING THE ISLAND OF IRELAND TO ITS WEST. THE ISLAND IS PART OF THE UNITED KINGDOM OF GREAT BRITAIN AND NORTHERN IRELAND, CONSTI-

ГОСУДАРСТВО РАСПОЛАГАЕТСЯ НА БРИТАНСКИХ ОСТРОВАХ (ОСТРОВ ВЕЛИКОБРИТАНИЯ, СЕВЕ-РО-ВОСТОЧНАЯ ЧАСТЬ ОСТРОВА ИРЛАНДИЯ, А ТАКЖЕ БОЛЬШОЕ КОЛИЧЕСТВО БОЛЕЕ МЕЛКИХ ОСТРОВОВ И АРХИПЕЛАГОВ. ОМЫВАЕТСЯ СЕВЕРНЫМ, ИРЛАНДСКИМ, КЕЛЬТСКИМ И ГЕБРИДСКИМ МОРЯМИ. **ПЛОЩАДЬ ВЕЛИКОБРИТАНИИ СОСТАВЛЯЕТ 243 809 КМ², ИЗ НИХ СУША — 240 579 КМ², ВНУТРЕННИЕ ВОДЫ — 3230 КМ².** ПО ДАННЫМ НА 1993 ГОД 10% СУШИ БЫЛИ ПОКРЫТЫ ЛЕСОМ, 46% ИСПОЛЬЗОВАЛИСЬ ПОД ПАСТБИЩА, А ЕЩЁ 25% ИСПОЛЬЗОВАЛОСЬ В ЗЕМЛЕДЕЛИИ. КАЖДАЯ СТРАНА СОЕДИНЁННОГО КОРОЛЕВСТВА ИМЕЕТ СВОЮ СОБСТВЕННУЮ СИСТЕМУ АДМИНИСТРАТИВНОГО И ГЕОГРАФИЧЕСКОГО ДЕЛЕНИЯ, КОТОРОЕ ЧАСТО ИСХОДИТ ЕЩЁ

Bering Stencil Condensed Thin, 6/8,5 pt

GREAT BRITAIN, ALSO KNOWN AS BRITAIN, IS AN ISLAND IN THE NORTH ATLANTIC OFF THE NORTH-WEST COAST OF CONTINENTAL EUROPE. WITH AN AREA OF 209,331 KM² (80,823 SQ MI), IT IS THE LARGEST ISLAND IN EUROPE AND THE NINTH-LARGEST IN THE WORLD. IN 2011 THE ISLAND HAD A POPULATION OF ABOUT 61 MILLION PEOPLE, MAKING IT THE THIRD-MOST POPULOUS ISLAND IN THE WORLD, AFTER JAVA IN INDONESIA AND HONSHU IN JAPAN. IT ACCOUNTS FOR THE MAJORITY OF THE BRITISH ISLES ARCHIPELAGO, ALONG WITH OVER 1,000 SMALLER SURROUNDING ISLANDS, INCLUDING THE ISLAND OF IRELAND TO ITS WEST. THE ISLAND IS PART OF THE UNITED KINGDOM OF GREAT BRITAIN AND NORTHERN IRELAND, CONSTITUTING MOST OF ITS TERRITORY: MOST OF ENGLAND, SCOTLAND, AND WALES ARE ON THE ISLAND, WITH THEIR RESPECTIVE CAPITAL CITIES, LONDON, EDINBURGH, AND CARDIFF. POLITICALLY, THE TERM GREAT BRITAIN USUALLY EXTENDS TO INCLUDE SURROUNDING ISLANDS THAT FORM PART OF ENGLAND, SCOTLAND, AND WALES. THE ISLAND IS DOMINATED BY AN OCEANIC CLIMATE WITH QUITE NARROW TEMPERATURE

ГОСУДАРСТВО РАСПОЛАГАЕТСЯ НА БРИТАНСКИХ ОСТРОВАХ (ОСТРОВ ВЕЛИКОБРИТАНИЯ, СЕВЕРО-ВОСТОЧНАЯ ЧАСТЬ ОСТРОВА ИРЛАНДИЯ, А ТАКЖЕ БОЛЬШОЕ КОЛИЧЕСТВО БОЛЕЕ МЕЛКИХ ОСТРОВОВ И АРХИПЕЛАГОВ, СРЕДИ КОТОРЫХ ГЕБРИДСКИЕ, ОРКНЕЙСКИЕ И ШЕТЛАНДСКИЕ ОСТРОВА, АНГЛСИ, АРРАН, УАЙТ) В АТЛАНТИЧЕСКОМ ОКЕАНЕ. ОМЫВАЕТСЯ СЕВЕРНЫМ, ИРЛАНДСКИМ, КЕЛЬТСКИМ И ГЕБРИДСКИМ МОРЯМИ. ЮГО-ВОСТОЧНОЕ ПОБЕРЕЖЬЕ РАСПОЛАГАЕТСЯ ВСЕГО В 35 КМ ОТ СЕВЕРНОГО ПОБЕРЕЖЬЯ ФРАНЦИИ, КОТОРЫЕ РАЗДЕЛЕНЫ ПРОЛИВОМ ЛА-МАНШ. ПЛОЩАДЬ ВЕЛИКОБРИТАНИИ СОСТАВЛЯЕТ 243 809 КМ², ИЗ НИХ СУША — 240 579 КМ², ВНУТРЕННИЕ ВОДЫ — 3230 КМ². ПО ДАННЫМ НА 1993 ГОД 10% СУШИ БЫЛИ ПОКРЫТЫ ЛЕСОМ, 46% ИСПОЛЬЗОВАЛИСЬ ПОД ПАСТБИЩА, А ЕЩЁ 25% ИСПОЛЬЗОВАЛОСЬ В ЗЕМЛЕДЕЛИИ. БЕРЕГОВАЯ ЛИНИЯ ИМЕЕТ 17 820 КМ ДЛИНЫ. ЮЖНОЕ ПОБЕРЕЖЬЕ СОЕДИНЕНО С КОНТИНЕНТАЛЬНОЙ ЕВРОПОЙ ЧЕРЕЗ ЕВРОТОННЕЛЬ ДЛИНОЙ 50 КМ (ИЗ КОТОРЫХ 38 КМ ПОД ВОДОЙ). ЭТО САМЫЙ ДЛИННЫЙ ПОДВОДНЫЙ ТОННЕЛЬ В МИРЕ. СЕВЕРНАЯ ИРЛАНДИЯ ИМЕЕТ 360-КИЛОМЕТРОВУЮ СУХОПУТНУЮ

Bering Stencil Condensed Thin, 8/10,5 pt

GREAT BRITAIN, ALSO KNOWN AS BRITAIN, IS AN ISLAND IN THE NORTH ATLANTIC OFF THE NORTH-WEST COAST OF CONTINENTAL EUROPE. WITH AN AREA OF 209,331 KM² (80,823 SQ MI), IT IS THE LARGEST ISLAND IN EUROPE AND THE NINTH-LARGEST IN THE WORLD. IN 2011 THE ISLAND HAD A POPULATION OF ABOUT 61 MILLION PEOPLE, MAKING IT THE THIRD-MOST POPULOUS ISLAND IN THE WORLD, AFTER JAVA IN INDONESIA AND HONSHU IN JAPAN. IT ACCOUNTS FOR THE MAJORITY OF THE BRITISH ISLES ARCHIPELAGO, ALONG WITH OVER 1,000 SMALLER SURROUNDING ISLANDS, INCLUDING THE ISLAND OF IRELAND TO ITS WEST. THE ISLAND IS PART OF THE UNITED KINGDOM OF GREAT BRITAIN AND NORTHERN IRELAND, CONSTITUTING MOST OF ITS TERRITORY: MOST OF

ГОСУДАРСТВО РАСПОЛАГАЕТСЯ НА БРИТАНСКИХ ОСТРОВАХ (ОСТРОВ ВЕЛИКОБРИТАНИЯ, СЕВЕРО-ВОСТОЧНАЯ ЧАСТЬ ОСТРОВА ИРЛАНДИЯ, А ТАКЖЕ БОЛЬШОЕ КОЛИЧЕСТВО БОЛЕЕ МЕЛКИХ ОСТРОВОВ И АРХИПЕЛАГОВ, СРЕДИ КОТОРЫХ ГЕБРИДСКИЕ, ОРКНЕЙСКИЕ И ШЕТЛАНДСКИЕ ОСТРОВА, АНГЛСИ, АРРАН, УАЙТ) В АТЛАНТИЧЕСКОМ ОКЕАНЕ. ОМЫВАЕТСЯ СЕВЕРНЫМ, ИРЛАНДСКИМ, КЕЛЬТСКИМ И ГЕБРИДСКИМ МОРЯМИ. ЮГО-ВОСТОЧНОЕ ПОБЕРЕЖЬЕ РАСПОЛАГАЕТСЯ ВСЕГО В 35 КМ ОТ СЕВЕРНОГО ПОБЕРЕЖЬЯ ФРАНЦИИ, КОТОРЫЕ РАЗДЕЛЕНЫ ПРОЛИВОМ ЛА-МАНШ. ПЛОЩАДЬ ВЕЛИКОБРИТАНИИ СОСТАВЛЯЕТ 243 809 КМ², ИЗ НИХ СУША — 240 579 КМ², ВНУТРЕННИЕ ВОДЫ — 3230 КМ². ПО ДАННЫМ НА 1993 ГОД 10% СУШИ БЫЛИ

Bering Stencil Condensed Thin, 10/13,5 pt

GREAT BRITAIN, ALSO KNOWN AS BRITAIN, IS AN ISLAND IN THE NORTH ATLANTIC OFF THE NORTH-WEST COAST OF CONTINENTAL EUROPE. WITH AN AREA OF 209,331 KM² (80,823 SQ MI), IT IS THE LARGEST ISLAND IN EUROPE AND THE NINTH-LARGEST IN THE WORLD. IN 2011 THE ISLAND HAD A POPULATION OF ABOUT 61 MILLION PEOPLE, MAKING IT THE THIRD-MOST POPULOUS ISLAND IN THE WORLD, AFTER JAVA IN INDONESIA AND HONSHU IN JAPAN. IT ACCOUNTS FOR THE MAJORITY OF THE BRITISH ISLES ARCHIPELAGO, ALONG WITH OVER 1,000 SMALLER SURROUNDING ISLANDS, INCLUDING THE ISLAND OF IRELAND TO ITS WEST. THE ISLAND IS PART OF THE UNITED KINGDOM OF GREAT BRITAIN AND NORTHERN IRELAND, CONSTITUTING MOST OF ITS TERRITORY: MOST OF ENGLAND, SCOTLAND, AND WALES ARE ON THE ISLAND, WITH THEIR RESPECTIVE CAPITAL CITIES, LONDON, EDINBURGH, AND CARDIFF. POLITICALLY, THE TERM GREAT BRITAIN USUALLY EXTENDS TO INCLUDE SURROUNDING ISLANDS THAT FORM PART OF ENGLAND, SCOTLAND, AND WALES. THE ISLAND IS DOMINATED BY AN OCEANIC CLIMATE WITH QUITE NARROW TEMPERATURE DIFFERENCES BETWEEN SEASONS. THE ROMANS CONQUERED MOST OF THE ISLAND (UP TO HADRIAN'S WALL, IN NORTHERN ENGLAND) AND THIS BECAME THE ANCIENT ROMAN PROVINCE OF BRITANNIA. IN THE COURSE OF THE 500 YEARS AFTER THE ROMAN EMPIRE

ГОСУДАРСТВО РАСПОЛАГАЕТСЯ НА БРИТАНСКИХ ОСТРОВАХ (ОСТРОВ ВЕЛИКОБРИТАНИЯ, СЕВЕРО-ВОСТОЧНАЯ ЧАСТЬ ОСТРОВА ИРЛАНДИЯ, А ТАКЖЕ БОЛЬШОЕ КОЛИЧЕСТВО БОЛЕЕ МЕЛКИХ ОСТРОВОВ И АРХИПЕЛАГОВ, СРЕДИ КОТОРЫХ ГЕБРИДСКИЕ, ОРКНЕЙСКИЕ И ШЕТЛАНДСКИЕ ОСТРОВА, АНГЛСИ, АРРАН, УАЙТ) В АТЛАНТИЧЕСКОМ ОКЕАНЕ. ОМЫВАЕТСЯ СЕВЕРНЫМ, ИРЛАНДСКИМ, КЕЛЬТСКИМ И ГЕБРИДСКИМ МОРЯМИ. ЮГО-ВОСТОЧНОЕ ПОБЕРЕЖЬЕ РАСПОЛАГАЕТСЯ ВСЕГО В 35 КМ ОТ СЕВЕРНОГО ПОБЕРЕЖЬЯ ФРАНЦИИ, КОТОРЫЕ РАЗДЕЛЕНЫ ПРОЛИВОМ ЛА-МАНШ. ПЛОЩАДЬ ВЕЛИКОБРИТАНИИ СОСТАВЛЯЕТ 243 809 КМ², ИЗ НИХ СУША — 240 579 КМ², ВНУТРЕННИЕ ВОДЫ — 3230 КМ². ПО ДАННЫМ НА 1993 ГОД 10% СУШИ БЫЛИ ПОКРЫТЫ ЛЕСОМ, 46% ИСПОЛЬЗОВАЛИСЬ ПОД ПАСТБИЩА, А ЕЩЁ 25% ИСПОЛЬЗОВАЛОСЬ В ЗЕМЛЕДЕЛИИ. ЮЖНОЕ ПОБЕРЕЖЬЕ СОЕДИНЕНО С КОНТИНЕНТАЛЬНОЙ ЕВРОПОЙ ЧЕРЕЗ ЕВРОТОННЕЛЬ ДЛИНОЙ 50 КМ (ИЗ КОТОРЫХ 38 КМ ПОД ВОДОЙ). ЭТО САМЫЙ ДЛИННЫЙ ПОДВОДНЫЙ ТОННЕЛЬ В МИРЕ. КАЖДАЯ СТРАНА СОЕДИНЁННОГО КОРОЛЕВСТВА ИМЕЕТ СВОЮ СОБСТВЕННУЮ СИСТЕМУ АДМИНИСТРАТИВНОГО И ГЕОГРАФИЧЕСКОГО ДЕЛЕНИЯ, КОТОРОЕ ЧАСТО ИСХОДИТ ЕЩЁ СО ВРЕМЁН ДО ПОЯВЛЕНИЯ ГОСУДАРСТВА ВЕЛИКОБРИТАНИЯ. СООТВЕТСТВЕННО «НЕ СУЩЕСТВУЕТ СТАНДАРТНОГО УРОВНЯ АДМИНИСТРАТИВНОЙ ЕДИНИЦЫ, СВЯЗЫВАЮЩЕГО ВСЮ ВЕЛИКОБРИТАНИЮ».

Bering Stencil Condensed Thin, 12/15,5 pt

GREAT BRITAIN, ALSO KNOWN AS BRITAIN, IS AN ISLAND IN THE NORTH ATLANTIC OFF THE NORTH-WEST COAST OF CONTINENTAL EUROPE. WITH AN AREA OF 209,331 KM² (80,823 SQ MI), IT IS THE LARGEST ISLAND IN EUROPE AND THE NINTH-LARGEST IN THE WORLD. IN 2011 THE ISLAND HAD A POPULATION OF ABOUT 61 MILLION PEOPLE, MAKING IT THE THIRD-MOST POPULOUS ISLAND IN THE WORLD, AFTER JAVA IN INDONESIA AND HONSHU IN JAPAN. IT ACCOUNTS FOR THE MAJORITY OF THE BRITISH ISLES ARCHIPELAGO, ALONG WITH OVER 1,000 SMALLER SURROUNDING ISLANDS, INCLUDING THE ISLAND OF IRELAND TO ITS WEST. THE ISLAND IS PART OF THE UNITED KINGDOM OF GREAT BRITAIN AND NORTHERN IRELAND, CONSTITUTING MOST OF ITS TERRITORY. THE ROMANS CONQUERED MOST OF THE ISLAND (UP TO HADRIAN'S WALL, IN NORTHERN ENGLAND) AND THIS BECAME THE ANCIENT ROMAN PROVINCE OF BRITANNIA. IN THE COURSE OF THE 500 YEARS AFTER THE ROMAN EMPIRE FELL, THE BRITONS OF THE SOUTH AND EAST OF THE ISLAND

ГОСУДАРСТВО РАСПОЛАГАЕТСЯ НА БРИТАНСКИХ ОСТРОВАХ (ОСТРОВ ВЕЛИКОБРИТАНИЯ, СЕВЕРО-ВОСТОЧНАЯ ЧАСТЬ ОСТРОВА ИРЛАНДИЯ, А ТАКЖЕ БОЛЬШОЕ КОЛИЧЕСТВО БОЛЕЕ МЕЛКИХ ОСТРОВОВ И АРХИПЕЛАГОВ. ОМЫВАЕТСЯ СЕВЕРНЫМ, ИРЛАНДСКИМ, КЕЛЬТСКИМ И ГЕБРИДСКИМ МОРЯМИ. ПЛОЩАДЬ ВЕЛИКОБРИТАНИИ СОСТАВЛЯЕТ 243 809 КМ², ИЗ НИХ СУША — 240 579 КМ², ВНУТРЕННИЕ ВОДЫ — 3230 КМ². ПО ДАННЫМ НА 1993 ГОД 10% СУШИ БЫЛИ ПОКРЫТЫ ЛЕСОМ, 46% ИСПОЛЬЗОВАЛИСЬ ПОД ПАСТБИЩА, А ЕЩЁ 25% ИСПОЛЬЗОВАЛОСЬ В ЗЕМЛЕДЕЛИИ. КАЖДАЯ СТРАНА СОЕДИНЁННОГО КОРОЛЕВСТВА ИМЕЕТ СВОЮ СОБСТВЕННУЮ СИСТЕМУ АДМИНИСТРАТИВНОГО И ГЕОГРАФИЧЕСКОГО ДЕЛЕНИЯ, КОТОРОЕ ЧАСТО ИСХОДИТ ЕЩЁ СО ВРЕМЁН ДО ПОЯВЛЕНИЯ ГОСУДАРСТВА ВЕЛИКОБРИТАНИЯ. СООТВЕТСТВЕННО «НЕ СУЩЕСТВУЕТ СТАНДАРТНОГО УРОВНЯ АДМИНИСТРАТИВНОЙ ЕДИНИЦЫ, СВЯЗЫВАЮЩЕГО ВСЮ ВЕЛИКОБРИТАНИЮ». ДО XIX ВЕКА ПРАКТИЧЕСКИ НИКАКИХ ИЗМЕНЕНИЙ СТАРЫХ ДЕЛЕНИЙ НЕ ПРОИСХОДИЛО, ОДНАКО ЗАТЕМ

Bering Stencil Condensed Light, 6/8,5 pt

GREAT BRITAIN, ALSO KNOWN AS BRITAIN, IS AN ISLAND IN THE NORTH ATLANTIC OFF THE NORTH-WEST COAST OF CONTINENTAL EUROPE. WITH AN AREA OF 209,331 KM² (80,823 SQ MI), IT IS THE LARGEST ISLAND IN EUROPE AND THE NINTH-LARGEST IN THE WORLD. IN 2011 THE ISLAND HAD A POPULATION OF ABOUT 61 MILLION PEOPLE, MAKING IT THE THIRD-MOST POPULOUS ISLAND IN THE WORLD, AFTER JAVA IN INDONESIA AND HONSHU IN JAPAN. IT ACCOUNTS FOR THE MAJORITY OF THE BRITISH ISLES ARCHIPELAGO, ALONG WITH OVER 1,000 SMALLER SURROUNDING ISLANDS, INCLUDING THE ISLAND OF IRELAND TO ITS WEST. THE ISLAND IS PART OF THE UNITED KINGDOM OF GREAT BRITAIN AND NORTHERN IRELAND, CONSTITUTING MOST OF ITS TERRITORY: MOST OF ENGLAND, SCOTLAND, AND WALES ARE ON THE ISLAND, WITH THEIR RESPECTIVE CAPITAL CITIES, LONDON, EDINBURGH, AND CARDIFF. POLITICALLY, THE TERM GREAT BRITAIN USUALLY EXTENDS TO INCLUDE SURROUNDING ISLANDS THAT FORM

ГОСУДАРСТВО РАСПОЛАГАЕТСЯ НА БРИТАНСКИХ ОСТРОВАХ (ОСТРОВ ВЕЛИКОБРИТАНИЯ, СЕВЕРО-ВОСТОЧНАЯ ЧАСТЬ ОСТРОВА ИРЛАНДИЯ, А ТАКЖЕ БОЛЬШОЕ КОЛИЧЕСТВО БОЛЕЕ МЕЛКИХ ОСТРОВОВ И АРХИПЕЛАГОВ, СРЕДИ КОТОРЫХ ГЕБРИДСКИЕ, ОРКНЕЙСКИЕ И ШЕТЛАНДСКИЕ ОСТРОВА, АНГЛСИ, АРРАН, УАЙТ) В АТЛАНТИЧЕСКОМ ОКЕАНЕ. ОМЫВАЕТСЯ СЕВЕРНЫМ, ИРЛАНДСКИМ, КЕЛЬТСКИМ И ГЕБРИДСКИМ МОРЯМИ. ЮГО-ВОСТОЧНОЕ ПОБЕРЕЖЬЕ РАСПОЛАГАЕТСЯ ВСЕГО В 35 КМ ОТ СЕВЕРНОГО ПОБЕРЕЖЬЯ ФРАНЦИИ, КОТОРЫЕ РАЗДЕЛЕНЫ ПРОЛИВОМ ЛА-МАНШ. ПЛОЩАДЬ ВЕЛИКОБРИТАНИИ СОСТАВЛЯЕТ 243 809 КМ², ИЗ НИХ СУША — 240 579 КМ², ВНУТРЕННИЕ ВОДЫ — 3230 КМ². ПО ДАННЫМ НА 1993 ГОД 10% СУШИ БЫЛИ ПОКРЫТЫ ЛЕСОМ, 46% ИСПОЛЬЗОВАЛИСЬ ПОД ПАСТБИЩА, А ЕЩЁ 25% ИСПОЛЬЗОВАЛОСЬ В ЗЕМЛЕДЕЛИИ. БЕРЕГОВАЯ ЛИНИЯ ИМЕЕТ 17 820 КМ ДЛИНЫ. ЮЖНОЕ ПОБЕРЕЖЬЕ СОЕДИНЕНО С КОНТИНЕНТАЛЬНОЙ ЕВРОПОЙ ЧЕРЕЗ ЕВРОТОННЕЛЬ ДЛИНОЙ 50 КМ (ИЗ КО-

Bering Stencil Condensed Light, 8/10,5 pt

GREAT BRITAIN, ALSO KNOWN AS BRITAIN, IS AN ISLAND IN THE NORTH ATLANTIC OFF THE NORTH-WEST COAST OF CONTINENTAL EUROPE. WITH AN AREA OF 209,331 KM² (80,823 SQ MI), IT IS THE LARGEST ISLAND IN EUROPE AND THE NINTH-LARGEST IN THE WORLD. IN 2011 THE ISLAND HAD A POPULATION OF ABOUT 61 MILLION PEOPLE, MAKING IT THE THIRD-MOST POPULOUS ISLAND IN THE WORLD, AFTER JAVA IN INDONESIA AND HONSHU IN JAPAN. IT ACCOUNTS FOR THE MAJORITY OF THE BRITISH ISLES ARCHIPELAGO, ALONG WITH OVER 1,000 SMALLER SURROUNDING ISLANDS, INCLUDING THE ISLAND OF IRELAND TO ITS WEST. THE ISLAND IS PART OF THE UNITED KINGDOM OF

ГОСУДАРСТВО РАСПОЛАГАЕТСЯ НА БРИТАНСКИХ ОСТРОВАХ (ОСТРОВ ВЕЛИКОБРИТАНИЯ, СЕВЕРО-ВОСТОЧНАЯ ЧАСТЬ ОСТРОВА ИРЛАНДИЯ, А ТАКЖЕ БОЛЬШОЕ КОЛИЧЕСТВО БОЛЕЕ МЕЛКИХ ОСТРОВОВ И АРХИПЕЛАГОВ, СРЕДИ КОТОРЫХ ГЕБРИДСКИЕ, ОРКНЕЙСКИЕ И ШЕТЛАНДСКИЕ ОСТРОВА, АНГЛСИ, АРРАН, УАЙТ) В АТЛАНТИЧЕСКОМ ОКЕАНЕ. ОМЫВАЕТСЯ СЕВЕРНЫМ, ИРЛАНДСКИМ, КЕЛЬТСКИМ И ГЕБРИДСКИМ МОРЯМИ. ЮГО-ВОСТОЧНОЕ ПОБЕРЕЖЬЕ РАСПОЛАГАЕТСЯ ВСЕГО В 35 КМ ОТ СЕВЕРНОГО ПОБЕРЕЖЬЯ ФРАНЦИИ, КОТОРЫЕ РАЗДЕЛЕНЫ ПРОЛИВОМ ЛА-МАНШ. ПЛОЩАДЬ ВЕЛИКОБРИТАНИИ СОСТАВЛЯЕТ 243 809 КМ², ИЗ НИХ

Bering Stencil Condensed Light, 10/13,5 pt

GREAT BRITAIN, ALSO KNOWN AS BRITAIN, IS AN ISLAND IN THE NORTH ATLANTIC OFF THE NORTH-WEST COAST OF CONTINENTAL EUROPE. WITH AN AREA OF 209,331 KM² (80,823 SQ MI), IT IS THE LARGEST ISLAND IN EUROPE AND THE NINTH-LARGEST IN THE WORLD. IN 2011 THE ISLAND HAD A POPULATION OF ABOUT 61 MILLION PEOPLE, MAKING IT THE THIRD-MOST POPULOUS ISLAND IN THE WORLD, AFTER JAVA IN INDONESIA AND HONSHU IN JAPAN. IT ACCOUNTS FOR THE MAJORITY OF THE BRITISH ISLES ARCHIPELAGO, ALONG WITH OVER 1,000 SMALLER SURROUNDING ISLANDS, INCLUDING THE ISLAND OF IRELAND TO ITS WEST. THE ISLAND IS PART OF THE UNITED KINGDOM OF GREAT BRITAIN AND NORTHERN IRELAND, CONSTITUTING MOST OF ITS TERRITORY: MOST OF ENGLAND, SCOTLAND, AND WALES ARE ON THE ISLAND, WITH THEIR RESPECTIVE CAPITAL CITIES, LONDON, EDINBURGH, AND CARDIFF. POLITICALLY, THE TERM GREAT BRITAIN USUALLY EXTENDS TO INCLUDE SURROUNDING ISLANDS THAT FORM PART OF ENGLAND, SCOTLAND, AND WALES. THE ISLAND IS DOMINATED BY AN OCEANIC CLIMATE WITH QUITE NARROW TEMPERATURE DIFFERENCES BETWEEN SEASONS. THE ROMANS CONQUERED MOST OF THE ISLAND (UP TO HADRIAN'S

ГОСУДАРСТВО РАСПОЛАГАЕТСЯ НА БРИТАНСКИХ ОСТРОВАХ (ОСТРОВ ВЕЛИКОБРИТАНИЯ, СЕВЕРО-ВОСТОЧНАЯ ЧАСТЬ ОСТРОВА ИРЛАНДИЯ, А ТАКЖЕ БОЛЬШОЕ КОЛИЧЕСТВО БОЛЕЕ МЕЛКИХ ОСТРОВОВ И АРХИПЕЛАГОВ, СРЕДИ КОТОРЫХ ГЕБРИДСКИЕ, ОРКНЕЙСКИЕ И ШЕТЛАНДСКИЕ ОСТРОВА, АНГЛСИ, АРРАН, УАЙТ) В АТЛАНТИЧЕСКОМ ОКЕАНЕ. ОМЫВАЕТСЯ СЕВЕРНЫМ, ИРЛАНДСКИМ, КЕЛЬТСКИМ И ГЕБРИДСКИМ МОРЯМИ. ЮГО-ВОСТОЧНОЕ ПОБЕРЕЖЬЕ РАСПОЛАГАЕТСЯ ВСЕГО В 35 КМ ОТ СЕВЕРНОГО ПОБЕРЕЖЬЯ ФРАНЦИИ, КОТОРЫЕ РАЗДЕЛЕНЫ ПРОЛИВОМ ЛА-МАНШ. ПЛОЩАДЬ ВЕЛИКОБРИТАНИИ СОСТАВЛЯЕТ 243 809 КМ², ИЗ НИХ СУША — 240 579 КМ², ВНУТРЕННИЕ ВОДЫ — 3230 КМ². ПО ДАННЫМ НА 1993 ГОД 10% СУШИ БЫЛИ ПОКРЫТЫ ЛЕСОМ, 46% ИСПОЛЬЗОВАЛИСЬ ПОД ПАСТБИЩА, А ЕЩЁ 25% ИСПОЛЬЗОВАЛОСЬ В ЗЕМЛЕДЕЛИИ. ЮЖНОЕ ПОБЕРЕЖЬЕ СОЕДИНЕНО С КОНТИНЕНТАЛЬНОЙ ЕВРОПОЙ ЧЕРЕЗ ЕВРОТОННЕЛЬ ДЛИНОЙ 50 КМ (ИЗ КОТОРЫХ 38 КМ ПОД ВОДОЙ). ЭТО САМЫЙ ДЛИННЫЙ ПОДВОДНЫЙ ТОННЕЛЬ В МИРЕ. КАЖДАЯ СТРАНА СОЕДИНЁННОГО КОРОЛЕВСТВА ИМЕЕТ СВОЮ СОБСТВЕННУЮ СИСТЕМУ АДМИНИСТРАТИВНОГО И ГЕОГРАФИЧЕСКОГО ДЕЛЕНИЯ, КОТОРОЕ ЧАСТО ИСХОДИТ ЕЩЁ СО ВРЕМЁН ДО ПОЯВЛЕНИЯ ГОСУДАР-

Bering Stencil Condensed Light, 12/15,5 pt

GREAT BRITAIN, ALSO KNOWN AS BRITAIN, IS AN ISLAND IN THE NORTH ATLANTIC OFF THE NORTH-WEST COAST OF CONTINENTAL EUROPE. WITH AN AREA OF 209,331 KM² (80,823 SQ MI), IT IS THE LARGEST ISLAND IN EUROPE AND THE NINTH-LARGEST IN THE WORLD. IN 2011 THE ISLAND HAD A POPULATION OF ABOUT 61 MILLION PEOPLE, MAKING IT THE THIRD-MOST POPULOUS ISLAND IN THE WORLD, AFTER JAVA IN INDONESIA AND HONSHU IN JAPAN. IT ACCOUNTS FOR THE MAJORITY OF THE BRITISH ISLES ARCHIPELAGO, ALONG WITH OVER 1,000 SMALLER SURROUNDING ISLANDS, INCLUDING THE ISLAND OF IRELAND TO ITS WEST. THE ISLAND IS PART OF THE UNITED KINGDOM OF GREAT BRITAIN AND NORTHERN IRELAND, CONSTITUTING MOST OF ITS TERRITORY. THE ROMANS CONQUERED MOST OF THE ISLAND (UP TO HADRIAN'S WALL, IN NORTHERN ENGLAND) AND THIS BECAME THE ANCIENT ROMAN PROVINCE OF BRITANNIA. IN THE

ГОСУДАРСТВО РАСПОЛАГАЕТСЯ НА БРИТАНСКИХ ОСТРОВАХ (ОСТРОВ ВЕЛИКОБРИТАНИЯ, СЕВЕРО-ВОСТОЧНАЯ ЧАСТЬ ОСТРОВА ИРЛАНДИЯ, А ТАКЖЕ БОЛЬШОЕ КОЛИЧЕСТВО БОЛЕЕ МЕЛКИХ ОСТРОВОВ И АРХИПЕЛАГОВ. ОМЫВАЕТСЯ СЕВЕРНЫМ, ИРЛАНДСКИМ, КЕЛЬТСКИМ И ГЕБРИДСКИМ МОРЯМИ. ПЛОЩАДЬ ВЕЛИКОБРИТАНИИ СОСТАВЛЯЕТ 243 809 КМ², ИЗ НИХ СУША — 240 579 КМ², ВНУТРЕННИЕ ВОДЫ — 3230 КМ². ПО ДАННЫМ НА 1993 ГОД 10% СУШИ БЫЛИ ПОКРЫТЫ ЛЕСОМ, 46% ИСПОЛЬЗОВАЛИСЬ ПОД ПАСТБИЩА, А ЕЩЁ 25% ИСПОЛЬЗОВАЛОСЬ В ЗЕМЛЕДЕЛИИ. КАЖДАЯ СТРАНА СОЕДИНЁННОГО КОРОЛЕВСТВА ИМЕЕТ СВОЮ СОБСТВЕННУЮ СИСТЕМУ АДМИНИСТРАТИВНОГО И ГЕОГРАФИЧЕСКОГО ДЕЛЕНИЯ, КОТОРОЕ ЧАСТО ИСХОДИТ ЕЩЁ СО ВРЕМЁН ДО ПОЯВЛЕНИЯ ГОСУДАРСТВА ВЕЛИКОБРИТАНИЯ. СООТВЕТСТВЕННО «НЕ СУЩЕСТВУЕТ СТАНДАРТНОГО УРОВНЯ АДМИНИСТРАТИВНОЙ ЕДИНИЦЫ, СВЯЗЫВАЮЩЕГО ВСЮ

Bering Stencil Condensed Regular, 6/8,5 pt

GREAT BRITAIN, ALSO KNOWN AS BRITAIN, IS AN ISLAND IN THE NORTH ATLANTIC OFF THE NORTH-WEST COAST OF CONTINENTAL EUROPE. WITH AN AREA OF 209,331 KM² (80,823 SQ MI), IT IS THE LARGEST ISLAND IN EUROPE AND THE NINTH-LARGEST IN THE WORLD. IN 2011 THE ISLAND HAD A POPULATION OF ABOUT 61 MILLION PEOPLE, MAKING IT THE THIRD-MOST POPULOUS ISLAND IN THE WORLD, AFTER JAVA IN INDONESIA AND HONSHU IN JAPAN. IT ACCOUNTS FOR THE MAJORITY OF THE BRITISH ISLES ARCHIPELAGO, ALONG WITH OVER 1,000 SMALLER SURROUNDING ISLANDS, INCLUDING THE ISLAND OF IRELAND TO ITS WEST. THE ISLAND IS PART OF THE UNITED KINGDOM OF GREAT BRITAIN AND NORTHERN IRELAND, CONSTITUTING MOST OF ITS TERRITORY: MOST OF ENGLAND, SCOTLAND, AND WALES ARE ON THE ISLAND, WITH THEIR RESPECTIVE CAPITAL CITIES, LONDON, EDINBURGH, AND CARDIFF. POLITICALLY,

ГОСУДАРСТВО РАСПОЛАГАЕТСЯ НА БРИТАНСКИХ ОСТРОВАХ (ОСТРОВ ВЕЛИКОБРИТАНИЯ, СЕВЕРО-ВОСТОЧНАЯ ЧАСТЬ ОСТРОВА ИРЛАНДИЯ, А ТАКЖЕ БОЛЬШОЕ КОЛИЧЕСТВО БОЛЕЕ МЕЛКИХ ОСТРОВОВ И АРХИПЕЛАГОВ, СРЕДИ КОТОРЫХ ГЕБРИДСКИЕ, ОРКНЕЙСКИЕ И ШЕТЛАНДСКИЕ ОСТРОВА, АНГЛСИ, АРРАН, УАЙТ) В АТЛАНТИЧЕСКОМ ОКЕАНЕ. ОМЫВАЕТСЯ СЕВЕРНЫМ, ИРЛАНДСКИМ, КЕЛЬТСКИМ И ГЕБРИДСКИМ МОРЯМИ. ЮГО-ВОСТОЧНОЕ ПОБЕРЕЖЬЕ РАСПОЛАГАЕТСЯ ВСЕГО В 35 КМ ОТ СЕВЕРНОГО ПОБЕРЕЖЬЯ ФРАНЦИИ, КОТОРЫЕ РАЗДЕЛЕНЫ ПРОЛИВОМ ЛА-МАНШ. ПЛОЩАДЬ ВЕЛИКОБРИТАНИИ СОСТАВЛЯЕТ 243 809 КМ², ИЗ НИХ СУША — 240 579 КМ², ВНУТРЕННИЕ ВОДЫ — 3230 КМ². ПО ДАННЫМ НА 1993 ГОД 10% СУШИ БЫЛИ ПОКРЫТЫ ЛЕСОМ, 46% ИСПОЛЬЗОВАЛИСЬ ПОД ПАСТБИЩА, А ЕЩЁ 25% ИСПОЛЬЗОВАЛОСЬ В ЗЕМЛЕДЕЛИИ. БЕРЕГОВАЯ ЛИНИЯ ИМЕЕТ 17 820 КМ

Bering Stencil Condensed Regular, 8/10,5 pt

GREAT BRITAIN, ALSO KNOWN AS BRITAIN, IS AN ISLAND IN THE NORTH ATLANTIC OFF THE NORTH-WEST COAST OF CONTINENTAL EUROPE. WITH AN AREA OF 209,331 KM² (80,823 SQ MI), IT IS THE LARGEST ISLAND IN EUROPE AND THE NINTH-LARGEST IN THE WORLD. IN 2011 THE ISLAND HAD A POPULATION OF ABOUT 61 MILLION PEOPLE, MAKING IT THE THIRD-MOST POPULOUS ISLAND IN THE WORLD, AFTER JAVA IN INDONESIA AND HONSHU IN JAPAN. IT ACCOUNTS FOR THE MAJORITY OF THE BRITISH ISLES ARCHIPELAGO, ALONG WITH OVER 1,000 SMALLER SURROUNDING ISLANDS, INCLUDING

ГОСУДАРСТВО РАСПОЛАГАЕТСЯ НА БРИТАНСКИХ ОСТРОВАХ (ОСТРОВ ВЕЛИКОБРИТАНИЯ, СЕВЕРО-ВОСТОЧНАЯ ЧАСТЬ ОСТРОВА ИРЛАНДИЯ, А ТАКЖЕ БОЛЬШОЕ КОЛИЧЕСТВО БОЛЕЕ МЕЛКИХ ОСТРОВОВ И АРХИПЕЛАГОВ, СРЕДИ КОТОРЫХ ГЕБРИДСКИЕ, ОРКНЕЙСКИЕ И ШЕТЛАНДСКИЕ ОСТРОВА, АНГЛСИ, АРРАН, УАЙТ) В АТЛАНТИЧЕСКОМ ОКЕАНЕ. ОМЫВАЕТСЯ СЕВЕРНЫМ, ИРЛАНДСКИМ, КЕЛЬТСКИМ И ГЕБРИДСКИМ МОРЯМИ. ЮГО-ВОСТОЧНОЕ ПОБЕРЕЖЬЕ РАСПОЛАГАЕТСЯ ВСЕГО В 35 КМ ОТ СЕВЕРНОГО ПОБЕРЕЖЬЯ ФРАНЦИИ, КОТОРЫЕ РАЗДЕЛЕНЫ ПРОЛИВОМ ЛА-МАНШ. ПЛОЩАДЬ

Bering Stencil Condensed Regular, 10/13,5 pt

GREAT BRITAIN, ALSO KNOWN AS BRITAIN, IS AN ISLAND IN THE NORTH ATLANTIC OFF THE NORTH-WEST COAST OF CONTINENTAL EUROPE. WITH AN AREA OF 209,331 KM² (80,823 SQ MI), IT IS THE LARGEST ISLAND IN EUROPE AND THE NINTH-LARGEST IN THE WORLD. IN 2011 THE ISLAND HAD A POPULATION OF ABOUT 61 MILLION PEOPLE, MAKING IT THE THIRD-MOST POPULOUS ISLAND IN THE WORLD, AFTER JAVA IN INDONESIA AND HONSHU IN JAPAN. IT ACCOUNTS FOR THE MAJORITY OF THE BRITISH ISLES ARCHIPELAGO, ALONG WITH OVER 1,000 SMALLER SURROUNDING ISLANDS, INCLUDING THE ISLAND OF IRELAND TO ITS WEST. THE ISLAND IS PART OF THE UNITED KINGDOM OF GREAT BRITAIN AND NORTHERN IRELAND, CONSTITUTING MOST OF ITS TERRITORY: MOST OF ENGLAND, SCOTLAND, AND WALES ARE ON THE ISLAND, WITH THEIR RESPECTIVE CAPITAL CITIES, LONDON, EDINBURGH, AND CARDIFF. POLITICALLY, THE TERM GREAT BRITAIN USUALLY EXTENDS TO INCLUDE SURROUNDING ISLANDS THAT FORM PART OF ENGLAND, SCOTLAND, AND WALES. THE ISLAND IS DOMINATED

ГОСУДАРСТВО РАСПОЛАГАЕТСЯ НА БРИТАНСКИХ ОСТРОВАХ (ОСТРОВ ВЕЛИКОБРИТАНИЯ, СЕВЕРО-ВОСТОЧНАЯ ЧАСТЬ ОСТРОВА ИРЛАНДИЯ, А ТАКЖЕ БОЛЬШОЕ КОЛИЧЕСТВО БОЛЕЕ МЕЛКИХ ОСТРОВОВ И АРХИПЕЛАГОВ, СРЕДИ КОТОРЫХ ГЕБРИДСКИЕ, ОРКНЕЙСКИЕ И ШЕТЛАНДСКИЕ ОСТРОВА, АНГЛСИ, АРРАН, УАЙТ) В АТЛАНТИЧЕСКОМ ОКЕАНЕ. ОМЫВАЕТСЯ СЕВЕРНЫМ, ИРЛАНДСКИМ, КЕЛЬТСКИМ И ГЕБРИДСКИМ МОРЯМИ. ЮГО-ВОСТОЧНОЕ ПОБЕРЕЖЬЕ РАСПОЛАГАЕТСЯ ВСЕГО В 35 КМ ОТ СЕВЕРНОГО ПОБЕРЕЖЬЯ ФРАНЦИИ, КОТОРЫЕ РАЗДЕЛЕНЫ ПРОЛИВОМ ЛА-МАНШ. ПЛОЩАДЬ ВЕЛИКОБРИТАНИИ СОСТАВЛЯЕТ 243 809 КМ², ИЗ НИХ СУША — 240 579 КМ², ВНУТРЕННИЕ ВОДЫ — 3230 КМ². ПО ДАННЫМ НА 1993 ГОД 10% СУШИ БЫЛИ ПОКРЫТЫ ЛЕСОМ, 46% ИСПОЛЬЗОВАЛИСЬ ПОД ПАСТБИЩА, А ЕЩЁ 25% ИСПОЛЬЗОВАЛОСЬ В ЗЕМЛЕДЕЛИИ. ЮЖНОЕ ПОБЕРЕЖЬЕ СОЕДИНЕНО С КОНТИНЕНТАЛЬНОЙ ЕВРОПОЙ ЧЕРЕЗ ЕВРОТОННЕЛЬ ДЛИНОЙ 50 КМ (ИЗ КОТОРЫХ 38 КМ ПОД ВОДОЙ). ЭТО САМЫЙ ДЛИННЫЙ ПОДВОДНЫЙ ТОННЕЛЬ В МИРЕ. КАЖДАЯ СТРАНА СОЕДИНЁННОГО КОРОЛЕВСТВА ИМЕЕТ СВОЮ СОБСТВЕННУЮ

Bering Stencil Condensed Regular, 12/15,5 pt

GREAT BRITAIN, ALSO KNOWN AS BRITAIN, IS AN ISLAND IN THE NORTH ATLANTIC OFF THE NORTH-WEST COAST OF CONTINENTAL EUROPE. WITH AN AREA OF 209,331 KM² (80,823 SQ MI), IT IS THE LARGEST ISLAND IN EUROPE AND THE NINTH-LARGEST IN THE WORLD. IN 2011 THE ISLAND HAD A POPULATION OF ABOUT 61 MILLION PEOPLE, MAKING IT THE THIRD-MOST POPULOUS ISLAND IN THE WORLD, AFTER JAVA IN INDONESIA AND HONSHU IN JAPAN. IT ACCOUNTS FOR THE MAJORITY OF THE BRITISH ISLES ARCHIPELAGO, ALONG WITH OVER 1,000 SMALLER SURROUNDING ISLANDS, INCLUDING THE ISLAND OF IRELAND TO ITS WEST. THE ISLAND IS PART OF THE UNITED KINGDOM OF GREAT BRITAIN AND NORTHERN IRELAND, CONSTITUTING MOST OF ITS TERRITORY. THE ROMANS CONQUERED MOST OF THE ISLAND (UP

ГОСУДАРСТВО РАСПОЛАГАЕТСЯ НА БРИТАНСКИХ ОСТРОВАХ (ОСТРОВ ВЕЛИКОБРИТАНИЯ, СЕВЕРО-ВОСТОЧНАЯ ЧАСТЬ ОСТРОВА ИРЛАНДИЯ, А ТАКЖЕ БОЛЬШОЕ КОЛИЧЕСТВО БОЛЕЕ МЕЛКИХ ОСТРОВОВ И АРХИПЕЛАГОВ. ОМЫВАЕТСЯ СЕВЕРНЫМ, ИРЛАНДСКИМ, КЕЛЬТСКИМ И ГЕБРИДСКИМ МОРЯМИ. ПЛОЩАДЬ ВЕЛИКОБРИТАНИИ СОСТАВЛЯЕТ 243 809 КМ², ИЗ НИХ СУША — 240 579 КМ², ВНУТРЕННИЕ ВОДЫ — 3230 КМ². ПО ДАННЫМ НА 1993 ГОД 10% СУШИ БЫЛИ ПОКРЫТЫ ЛЕСОМ, 46% ИСПОЛЬЗОВАЛИСЬ ПОД ПАСТБИЩА, А ЕЩЁ 25% ИСПОЛЬЗОВАЛОСЬ В ЗЕМЛЕДЕЛИИ. КАЖДАЯ СТРАНА СОЕДИНЁННОГО КОРОЛЕВСТВА ИМЕЕТ СВОЮ СОБСТВЕННУЮ СИСТЕМУ АДМИНИСТРАТИВНОГО И ГЕОГРАФИЧЕСКОГО ДЕЛЕНИЯ, КОТОРОЕ ЧАСТО ИСХОДИТ ЕЩЁ СО ВРЕМЁН ДО ПОЯВЛЕНИЯ ГОСУДАРСТВА ВЕЛИКОБРИТАНИЯ. СООТВЕТ-

Bering Stencil Condensed Bold, 6/8,5 pt

GREAT BRITAIN, ALSO KNOWN AS BRITAIN, IS AN ISLAND IN THE NORTH ATLANTIC OFF THE NORTH-WEST COAST OF CONTINENTAL EUROPE. WITH AN AREA OF 209,331 KM² (80,823 SQ MI), IT IS THE LARGEST ISLAND IN EUROPE AND THE NINTH-LARGEST IN THE WORLD. IN 2011 THE ISLAND HAD A POPULATION OF ABOUT 61 MILLION PEOPLE, MAKING IT THE THIRD-MOST POPULOUS ISLAND IN THE WORLD, AFTER JAVA IN INDONESIA AND HONSHU IN JAPAN. IT ACCOUNTS FOR THE MAJORITY OF THE BRITISH ISLES ARCHIPELAGO, ALONG WITH OVER 1,000 SMALLER SURROUNDING ISLANDS, INCLUDING THE ISLAND OF IRELAND TO ITS WEST. THE ISLAND IS PART OF THE UNITED KINGDOM OF GREAT BRITAIN AND NORTHERN IRELAND, CONSTITUTING MOST OF ITS TERRITORY: MOST OF ENGLAND, SCOTLAND, AND WALES ARE ON

ГОСУДАРСТВО РАСПОЛАГАЕТСЯ НА БРИТАНСКИХ ОСТРОВАХ (ОСТРОВ ВЕЛИКОБРИТАНИЯ, СЕВЕРО-ВОСТОЧНАЯ ЧАСТЬ ОСТРОВА ИРЛАНДИЯ, А ТАКЖЕ БОЛЬШОЕ КОЛИЧЕСТВО БОЛЕЕ МЕЛКИХ ОСТРОВОВ И АРХИПЕЛАГОВ, СРЕДИ КОТОРЫХ ГЕБРИДСКИЕ, ОРКНЕЙСКИЕ И ШЕТЛАНДСКИЕ ОСТРОВА, АНГЛСИ, АРРАН, УАЙТ) В АТЛАНТИЧЕСКОМ ОКЕАНЕ. ОМЫВАЕТСЯ СЕВЕРНЫМ, ИРЛАНДСКИМ, КЕЛЬТСКИМ И ГЕБРИДСКИМ МОРЯМИ. ЮГО-ВОСТОЧНОЕ ПОБЕРЕЖЬЕ РАСПОЛАГАЕТСЯ ВСЕГО В 35 КМ ОТ СЕВЕРНОГО ПОБЕРЕЖЬЯ ФРАНЦИИ, КОТОРЫЕ РАЗДЕЛЕНЫ ПРОЛИВОМ ЛА-МАНШ. ПЛОЩАДЬ ВЕЛИКОБРИТАНИИ СОСТАВЛЯЕТ 243 809 КМ², ИЗ НИХ СУША — 240 579 КМ², ВНУТРЕННИЕ ВОДЫ — 3230 КМ². ПО ДАННЫМ НА 1993 ГОД 10% СУШИ БЫЛИ ПОКРЫТЫ ЛЕСОМ, 46% ИСПОЛЬЗОВАЛИСЬ ПОД ПАСТБИЩА, А ЕЩЁ 25%

Bering Stencil Condensed Bold, 8/10,5 pt

GREAT BRITAIN, ALSO KNOWN AS BRITAIN, IS AN ISLAND IN THE NORTH ATLANTIC OFF THE NORTH-WEST COAST OF CONTINENTAL EUROPE. WITH AN AREA OF 209,331 KM² (80,823 SQ MI), IT IS THE LARGEST ISLAND IN EUROPE AND THE NINTH-LARGEST IN THE WORLD. IN 2011 THE ISLAND HAD A POPULATION OF ABOUT 61 MILLION PEOPLE, MAKING IT THE THIRD-MOST POPULOUS ISLAND IN THE WORLD, AFTER JAVA IN INDONESIA AND HONSHU IN JAPAN. IT ACCOUNTS FOR THE MAJORITY OF THE BRITISH ISLES ARCHIPELAGO, ALONG WITH OVER 1,000 SMALLER

ГОСУДАРСТВО РАСПОЛАГАЕТСЯ НА БРИТАНСКИХ ОСТРОВАХ (ОСТРОВ ВЕЛИКОБРИТАНИЯ, СЕВЕРО-ВОСТОЧНАЯ ЧАСТЬ ОСТРОВА ИРЛАНДИЯ, А ТАКЖЕ БОЛЬШОЕ КОЛИЧЕСТВО БОЛЕЕ МЕЛКИХ ОСТРОВОВ И АРХИПЕЛАГОВ, СРЕДИ КОТОРЫХ ГЕБРИДСКИЕ, ОРКНЕЙСКИЕ И ШЕТЛАНДСКИЕ ОСТРОВА, АНГЛСИ, АРРАН, УАЙТ) В АТЛАНТИЧЕСКОМ ОКЕАНЕ. ОМЫВАЕТСЯ СЕВЕРНЫМ, ИРЛАНДСКИМ, КЕЛЬТСКИМ И ГЕБРИДСКИМ МОРЯМИ. ЮГО-ВОСТОЧНОЕ ПОБЕРЕЖЬЕ РАСПОЛАГАЕТСЯ ВСЕГО В 35 КМ ОТ СЕВЕРНОГО ПОБЕРЕЖЬЯ ФРАНЦИИ, КОТОРЫЕ РАЗДЕЛЕНЫ

Bering Stencil Condensed Bold, 10/13,5 pt

GREAT BRITAIN, ALSO KNOWN AS BRITAIN, IS AN ISLAND IN THE NORTH ATLANTIC OFF THE NORTH-WEST COAST OF CONTINENTAL EUROPE. WITH AN AREA OF 209,331 KM² (80,823 SQ MI), IT IS THE LARGEST ISLAND IN EUROPE AND THE NINTH-LARGEST IN THE WORLD. IN 2011 THE ISLAND HAD A POPULATION OF ABOUT 61 MILLION PEOPLE, MAKING IT THE THIRD-MOST POPULOUS ISLAND IN THE WORLD, AFTER JAVA IN INDONESIA AND HONSHU IN JAPAN. IT ACCOUNTS FOR THE MAJORITY OF THE BRITISH ISLES ARCHIPELAGO, ALONG WITH OVER 1,000 SMALLER SURROUNDING ISLANDS, INCLUDING THE ISLAND OF IRELAND TO ITS WEST. THE ISLAND IS PART OF THE UNITED KINGDOM OF GREAT BRITAIN AND NORTHERN IRELAND, CONSTITUTING MOST OF ITS TERRITORY: MOST OF ENGLAND, SCOTLAND, AND WALES ARE ON THE ISLAND, WITH THEIR RESPECTIVE CAPITAL CITIES, LONDON, EDINBURGH, AND CARDIFF. POLITICALLY, THE TERM GREAT BRITAIN USUALLY EXTENDS TO INCLUDE SURROUNDING

ГОСУДАРСТВО РАСПОЛАГАЕТСЯ НА БРИТАНСКИХ ОСТРОВАХ (ОСТРОВ ВЕЛИКОБРИТАНИЯ, СЕВЕРО-ВОСТОЧНАЯ ЧАСТЬ ОСТРОВА ИРЛАНДИЯ, А ТАКЖЕ БОЛЬШОЕ КОЛИЧЕСТВО БОЛЕЕ МЕЛКИХ ОСТРОВОВ И АРХИПЕЛАГОВ, СРЕДИ КОТОРЫХ ГЕБРИДСКИЕ, ОРКНЕЙСКИЕ И ШЕТЛАНДСКИЕ ОСТРОВА, АНГЛСИ, АРРАН, УАЙТ) В АТЛАНТИЧЕСКОМ ОКЕАНЕ. ОМЫВАЕТСЯ СЕВЕРНЫМ, ИРЛАНДСКИМ, КЕЛЬТСКИМ И ГЕБРИДСКИМ МОРЯМИ. ЮГО-ВОСТОЧНОЕ ПОБЕРЕЖЬЕ РАСПОЛАГАЕТСЯ ВСЕГО В 35 КМ ОТ СЕВЕРНОГО ПОБЕРЕЖЬЯ ФРАНЦИИ, КОТОРЫЕ РАЗДЕЛЕНЫ ПРОЛИВОМ ЛА-МАНШ. ПЛОЩАДЬ ВЕЛИКОБРИТАНИИ СОСТАВЛЯЕТ 243 809 КМ², ИЗ НИХ СУША — 240 579 КМ², ВНУТРЕННИЕ ВОДЫ — 3230 КМ². ПО ДАННЫМ НА 1993 ГОД 10% СУШИ БЫЛИ ПОКРЫТЫ ЛЕСОМ, 46% ИСПОЛЬЗОВАЛИСЬ ПОД ПАСТБИЩА, А ЕЩЁ 25% ИСПОЛЬЗОВАЛОСЬ В ЗЕМЛЕДЕЛИИ. ЮЖНОЕ ПОБЕРЕЖЬЕ СОЕДИНЕНО С КОНТИНЕНТАЛЬНОЙ ЕВРОПОЙ ЧЕРЕЗ ЕВРОТОННЕЛЬ ДЛИНОЙ 50 КМ (ИЗ КОТОРЫХ 38 КМ ПОД ВОДОЙ). ЭТО САМЫЙ

Bering Stencil Condensed Bold, 12/15,5 pt

GREAT BRITAIN, ALSO KNOWN AS BRITAIN, IS AN ISLAND IN THE NORTH ATLANTIC OFF THE NORTH-WEST COAST OF CONTINENTAL EUROPE. WITH AN AREA OF 209,331 KM² (80,823 SQ MI), IT IS THE LARGEST ISLAND IN EUROPE AND THE NINTH-LARGEST IN THE WORLD. IN 2011 THE ISLAND HAD A POPULATION OF ABOUT 61 MILLION PEOPLE, MAKING IT THE THIRD-MOST POPULOUS ISLAND IN THE WORLD, AFTER JAVA IN INDONESIA AND HONSHU IN JAPAN. IT ACCOUNTS FOR THE MAJORITY OF THE BRITISH ISLES ARCHIPELAGO, ALONG WITH OVER 1,000 SMALLER SURROUNDING ISLANDS, INCLUDING THE ISLAND OF IRELAND TO ITS WEST. THE ISLAND IS PART OF THE UNITED KINGDOM OF GREAT BRITAIN AND NORTHERN IRELAND,

ГОСУДАРСТВО РАСПОЛАГАЕТСЯ НА БРИТАНСКИХ ОСТРОВАХ (ОСТРОВ ВЕЛИКОБРИТАНИЯ, СЕВЕРО-ВОСТОЧНАЯ ЧАСТЬ ОСТРОВА ИРЛАНДИЯ, А ТАКЖЕ БОЛЬШОЕ КОЛИЧЕСТВО БОЛЕЕ МЕЛКИХ ОСТРОВОВ И АРХИПЕЛАГОВ. ОМЫВАЕТСЯ СЕВЕРНЫМ, ИРЛАНДСКИМ, КЕЛЬТСКИМ И ГЕБРИДСКИМ МОРЯМИ. ПЛОЩАДЬ ВЕЛИКОБРИТАНИИ СОСТАВЛЯЕТ 243 809 КМ², ИЗ НИХ СУША — 240 579 КМ², ВНУТРЕННИЕ ВОДЫ — 3230 КМ². ПО ДАННЫМ НА 1993 ГОД 10% СУШИ БЫЛИ ПОКРЫТЫ ЛЕСОМ, 46% ИСПОЛЬЗОВАЛИСЬ ПОД ПАСТБИЩА, А ЕЩЁ 25% ИСПОЛЬЗОВАЛОСЬ В ЗЕМЛЕДЕЛИИ. КАЖДАЯ СТРАНА СОЕДИНЁННОГО КОРОЛЕВСТВА ИМЕЕТ СВОЮ СОБСТВЕННУЮ СИСТЕМУ АДМИНИСТРАТИВНОГО И ГЕОГРАФИЧЕСКОГО ДЕЛЕНИЯ, КОТОРОЕ ЧАСТО ИСХОДИТ

Bering Stencil Condensed Light, Bold, 6/8,5 pt

GREAT BRITAIN, ALSO KNOWN AS BRITAIN, IS AN ISLAND IN THE NORTH ATLANTIC OFF THE NORTH-WEST COAST OF CONTINENTAL EUROPE. WITH AN AREA OF 209,331 KM² (80,823 SQ MI), IT IS THE LARGEST ISLAND IN EUROPE AND THE NINTH-LARGEST IN THE WORLD. IN 2011 THE ISLAND HAD A POPULATION OF ABOUT 61 MILLION PEOPLE, MAKING IT THE THIRD-MOST POPULOUS ISLAND IN THE WORLD, AFTER JAVA IN INDONESIA AND HONSHU IN JAPAN. **IT ACCOUNTS FOR THE MAJORITY OF THE BRITISH ISLES ARCHIPELAGO, ALONG WITH OVER 1,000 SMALLER SURROUNDING ISLANDS, INCLUDING THE ISLAND OF IRELAND TO ITS WEST.** THE ISLAND IS PART OF THE UNITED KINGDOM OF GREAT BRITAIN AND NORTHERN IRELAND, CONSTITUTING MOST OF ITS TERRITORY: MOST OF ENGLAND, SCOTLAND, AND WALES ARE ON THE ISLAND, WITH THEIR RESPECTIVE CAPITAL CITIES, LONDON, EDINBURGH, AND CARDIFF. POLITICALLY, THE TERM GREAT BRITAIN USUALLY EXTENDS TO INCLUDE

ГОСУДАРСТВО РАСПОЛАГАЕТСЯ НА БРИТАНСКИХ ОСТРОВАХ (ОСТРОВ ВЕЛИКОБРИТАНИЯ, СЕВЕРО-ВОСТОЧНАЯ ЧАСТЬ ОСТРОВА ИРЛАНДИЯ, А ТАКЖЕ БОЛЬШОЕ КОЛИЧЕСТВО БОЛЕЕ МЕЛКИХ ОСТРОВОВ И АРХИПЕЛАГОВ, СРЕДИ КОТОРЫХ ГЕБРИДСКИЕ, ОРКНЕЙСКИЕ И ШЕТЛАНДСКИЕ ОСТРОВА, АНГЛСИ, АРРАН, УАЙТ) В АТЛАНТИЧЕСКОМ ОКЕАНЕ. ОМЫВАЕТСЯ СЕВЕРНЫМ, ИРЛАНДСКИМ, КЕЛЬТСКИМ И ГЕБРИДСКИМ МОРЯМИ. **ЮГО-ВОСТОЧНОЕ ПОБЕРЕЖЬЕ РАСПОЛАГАЕТСЯ ВСЕГО В 35 КМ ОТ СЕВЕРНОГО ПОБЕРЕЖЬЯ ФРАНЦИИ, КОТОРЫЕ РАЗДЕЛЕНЫ ПРОЛИВОМ ЛА-МАНШ.** ПЛОЩАДЬ ВЕЛИКОБРИТАНИИ СОСТАВЛЯЕТ 243 809 КМ², ИЗ НИХ СУША — 240 579 КМ², ВНУТРЕННИЕ ВОДЫ — 3230 КМ². ПО ДАННЫМ НА 1993 ГОД 10% СУШИ БЫЛИ ПОКРЫТЫ ЛЕСОМ, 46% ИСПОЛЬЗОВАЛИСЬ ПОД ПАСТБИЩА, А ЕЩЁ 25% ИСПОЛЬЗОВАЛОСЬ В ЗЕМЛЕДЕЛИИ. БЕРЕГОВАЯ ЛИНИЯ ИМЕЕТ 17 820 КМ ДЛИНЫ. ЮЖНОЕ ПОБЕРЕЖЬЕ СОЕДИНЕНО С КОНТИНЕНТАЛЬНОЙ ЕВРОПОЙ ЧЕРЕЗ

Bering Stencil Condensed Light, Bold, 8/10,5 pt

GREAT BRITAIN, ALSO KNOWN AS BRITAIN, IS AN ISLAND IN THE NORTH ATLANTIC OFF THE NORTH-WEST COAST OF CONTINENTAL EUROPE. WITH AN AREA OF 209,331 KM² (80,823 SQ MI), **IT IS THE LARGEST ISLAND IN EUROPE AND THE NINTH-LARGEST IN THE WORLD.** IN 2011 THE ISLAND HAD A POPULATION OF ABOUT 61 MILLION PEOPLE, MAKING IT THE THIRD-MOST POPULOUS ISLAND IN THE WORLD, AFTER JAVA IN INDONESIA AND HONSHU IN JAPAN. IT ACCOUNTS FOR THE MAJORITY OF THE BRITISH ISLES ARCHIPELAGO, ALONG WITH OVER 1,000 SMALLER SURROUNDING ISLANDS, INCLUDING THE ISLAND OF IRELAND TO ITS WEST. THE

ГОСУДАРСТВО РАСПОЛАГАЕТСЯ НА БРИТАНСКИХ ОСТРОВАХ (ОСТРОВ ВЕЛИКОБРИТАНИЯ, СЕВЕРО-ВОСТОЧНАЯ ЧАСТЬ ОСТРОВА ИРЛАНДИЯ, **А ТАКЖЕ БОЛЬШОЕ КОЛИЧЕСТВО БОЛЕЕ МЕЛКИХ ОСТРОВОВ И АРХИПЕЛАГОВ,** СРЕДИ КОТОРЫХ ГЕБРИДСКИЕ, ОРКНЕЙСКИЕ И ШЕТЛАНДСКИЕ ОСТРОВА, АНГЛСИ, АРРАН, УАЙТ) В АТЛАНТИЧЕСКОМ ОКЕАНЕ. ОМЫВАЕТСЯ СЕВЕРНЫМ, ИРЛАНДСКИМ, КЕЛЬТСКИМ И ГЕБРИДСКИМ МОРЯМИ. **ЮГО-ВОСТОЧНОЕ ПОБЕРЕЖЬЕ** РАСПОЛАГАЕТСЯ ВСЕГО В 35 КМ ОТ СЕВЕРНОГО ПОБЕРЕЖЬЯ ФРАНЦИИ, КОТОРЫЕ РАЗДЕЛЕНЫ ПРОЛИВОМ ЛА-МАНШ. ПЛОЩАДЬ ВЕЛИКОБРИТАНИИ СОСТАВЛЯЕТ 243 809 КМ², ИЗ НИХ

Bering Stencil Condensed Light, Bold, 10/13,5 pt

GREAT BRITAIN, ALSO KNOWN AS BRITAIN, IS AN ISLAND IN THE NORTH ATLANTIC OFF THE NORTH-WEST COAST OF CONTINENTAL EUROPE. WITH AN AREA OF 209,331 KM² (80,823 SQ MI), IT IS THE LARGEST ISLAND IN EUROPE AND THE NINTH-LARGEST IN THE WORLD. **IN 2011 THE ISLAND HAD A POPULATION OF ABOUT 61 MILLION PEOPLE, MAKING IT THE THIRD-MOST POPULOUS ISLAND IN THE WORLD, AFTER JAVA IN INDONESIA AND HONSHU IN JAPAN.** IT ACCOUNTS FOR THE MAJORITY OF THE BRITISH ISLES ARCHIPELAGO, ALONG WITH OVER 1,000 SMALLER SURROUNDING ISLANDS, INCLUDING THE ISLAND OF IRELAND TO ITS WEST. THE ISLAND IS PART OF THE UNITED KINGDOM OF GREAT BRITAIN AND NORTHERN IRELAND, CONSTITUTING MOST OF ITS TERRITORY: MOST OF ENGLAND, SCOTLAND, AND WALES ARE ON THE ISLAND, **WITH THEIR RESPECTIVE CAPITAL CITIES, LONDON, EDINBURGH, AND CARDIFF.** POLITICALLY, THE TERM GREAT BRITAIN USUALLY EXTENDS TO INCLUDE SURROUNDING ISLANDS THAT FORM PART OF ENGLAND, SCOTLAND, AND WALES. THE ISLAND IS DOMINATED BY AN OCEANIC CLIMATE WITH QUITE NARROW TEMPERATURE DIFFERENCES BETWEEN SEASONS.

ГОСУДАРСТВО РАСПОЛАГАЕТСЯ НА БРИТАНСКИХ ОСТРОВАХ (ОСТРОВ ВЕЛИКОБРИТАНИЯ, СЕВЕРО-ВОСТОЧНАЯ ЧАСТЬ ОСТРОВА ИРЛАНДИЯ, А ТАКЖЕ БОЛЬШОЕ КОЛИЧЕСТВО БОЛЕЕ МЕЛКИХ ОСТРОВОВ И АРХИПЕЛАГОВ, СРЕДИ КОТОРЫХ ГЕБРИДСКИЕ, ОРКНЕЙСКИЕ И ШЕТЛАНДСКИЕ ОСТРОВА, АНГЛСИ, АРРАН, УАЙТ) В АТЛАНТИЧЕСКОМ ОКЕАНЕ. ОМЫВАЕТСЯ СЕВЕРНЫМ, ИРЛАНДСКИМ, КЕЛЬТСКИМ И ГЕБРИДСКИМ МОРЯМИ. ЮГО-ВОСТОЧНОЕ ПОБЕРЕЖЬЕ РАСПОЛАГАЕТСЯ ВСЕГО В 35 КМ ОТ СЕВЕРНОГО ПОБЕРЕЖЬЯ ФРАНЦИИ, КОТОРЫЕ РАЗДЕЛЕНЫ ПРОЛИВОМ ЛА-МАНШ. **ПЛОЩАДЬ ВЕЛИКОБРИТАНИИ СОСТАВЛЯЕТ 243 809 КМ², ИЗ НИХ СУША — 240 579 КМ², ВНУТРЕННИЕ ВОДЫ — 3230 КМ². ПО ДАННЫМ НА 1993 ГОД 10% СУШИ БЫЛИ ПОКРЫТЫ ЛЕСОМ, 46% ИСПОЛЬЗОВАЛИСЬ ПОД ПАСТБИЩА, А ЕЩЁ 25% ИСПОЛЬЗОВАЛОСЬ В ЗЕМЛЕДЕЛИИ.** ЮЖНОЕ ПОБЕРЕЖЬЕ СОЕДИНЕНО С КОНТИНЕНТАЛЬНОЙ ЕВРОПОЙ ЧЕРЕЗ ЕВРОТОННЕЛЬ ДЛИНОЙ 50 КМ (ИЗ КОТОРЫХ 38 КМ ПОД ВОДОЙ). ЭТО САМЫЙ ДЛИННЫЙ ПОДВОДНЫЙ ТОННЕЛЬ В МИРЕ. КАЖДАЯ СТРАНА СОЕДИНЁННОГО КОРОЛЕВСТВА ИМЕЕТ СВОЮ СОБСТВЕННУЮ СИСТЕМУ АДМИНИСТРАТИВНОГО И ГЕОГРАФИЧЕСКОГО

Bering Stencil Condensed Light, Bold, 12/15,5 pt

GREAT BRITAIN, ALSO KNOWN AS BRITAIN, IS AN ISLAND IN THE NORTH ATLANTIC OFF THE NORTH-WEST COAST OF CONTINENTAL EUROPE. WITH AN AREA OF 209,331 KM² (80,823 SQ MI), IT IS THE LARGEST ISLAND IN EUROPE AND THE NINTH-LARGEST IN THE WORLD. **IN 2011 THE ISLAND HAD A POPULATION OF ABOUT 61 MILLION PEOPLE, MAKING IT THE THIRD-MOST POPULOUS ISLAND IN THE WORLD, AFTER JAVA IN INDONESIA AND HONSHU IN JAPAN.** IT ACCOUNTS FOR THE MAJORITY OF THE BRITISH ISLES ARCHIPELAGO, ALONG WITH OVER 1,000 SMALLER SURROUNDING ISLANDS, INCLUDING THE ISLAND OF IRELAND TO ITS WEST. THE ISLAND IS PART OF THE UNITED KINGDOM OF GREAT BRITAIN AND NORTHERN IRELAND, CONSTITUTING MOST OF ITS TERRITORY. THE ROMANS CONQUERED MOST OF THE ISLAND (UP TO HADRIAN'S WALL, IN NORTHERN ENGLAND) AND

ГОСУДАРСТВО РАСПОЛАГАЕТСЯ НА БРИТАНСКИХ ОСТРОВАХ (ОСТРОВ ВЕЛИКОБРИТАНИЯ, СЕВЕРО-ВОСТОЧНАЯ ЧАСТЬ ОСТРОВА ИРЛАНДИЯ, А ТАКЖЕ БОЛЬШОЕ КОЛИЧЕСТВО БОЛЕЕ МЕЛКИХ ОСТРОВОВ И АРХИПЕЛАГОВ. ОМЫВАЕТСЯ СЕВЕРНЫМ, ИРЛАНДСКИМ, КЕЛЬТСКИМ И ГЕБРИДСКИМ МОРЯМИ. ПЛОЩАДЬ ВЕЛИКОБРИТАНИИ СОСТАВЛЯЕТ 243 809 КМ², ИЗ НИХ СУША — 240 579 КМ², ВНУТРЕННИЕ ВОДЫ — 3230 КМ². **ПО ДАННЫМ НА 1993 ГОД 10% СУШИ БЫЛИ ПОКРЫТЫ ЛЕСОМ, 46% ИСПОЛЬЗОВАЛИСЬ ПОД ПАСТБИЩА, А ЕЩЁ 25% ИСПОЛЬЗОВАЛОСЬ В ЗЕМЛЕДЕЛИИ.** КАЖДАЯ СТРАНА СОЕДИНЁННОГО КОРОЛЕВСТВА ИМЕЕТ СВОЮ СОБСТВЕННУЮ СИСТЕМУ АДМИНИСТРАТИВНОГО И ГЕОГРАФИЧЕСКОГО ДЕЛЕНИЯ, КОТОРОЕ ЧАСТО ИСХОДИТ ЕЩЁ СО ВРЕМЁН ДО ПОЯВЛЕНИЯ ГОСУДАРСТВА ВЕЛИКОБРИТАНИЯ. СООТВЕТСТВЕННО «НЕ СУЩЕСТВУЕТ СТАНДАРТНОГО УРОВНЯ

Bering Stencil Regular, 11/13,5 pt

Français

QUOIQUE CE DÉTAIL NE TOUCHE EN AUCUNE MANIÈRE AU FOND MÊME DE CE QUE NOUS AVONS À RACONTER, IL N'EST PEUT-ÊTRE PAS INUTILE, NE FÛT-CE QUE POUR ÊTRE EXACT EN TOUT, D'INDIQUER ICI LES BRUITS ET LES PROPOS QUI AVAIENT COURU SUR SON COMPTE AU MOMENT OÙ IL ÉTAIT ARRIVÉ DANS LE DIOCÈSE. VRAI OU FAUX, CE QU'ON DIT DES HOMMES TIENT SOUVENT AUTANT DE PLACE DANS LEUR VIE ET SURTOUT DANS LEUR DESTINÉE QUE CE QU'ILS FONT. M. MYRIEL ÉTAIT FILS D'UN CONSEILLER AU PARLEMENT D'AIX; NOBLESSE DE ROBE. ON CONTAIT DE LUI QUE SON PÈRE, LE RÉSERVANT POUR HÉRITER DE SA CHARGE, L'AVAIT MARIÉ DE FORT BONNE HEURE, À DIX-HUIT OU VINGT ANS, SUIVANT UN USAGE ASSEZ RÉPANDU DANS LES FAMILLES PARLEMENTAIRES. CHARLES MYRIEL, NONOBSTANT CE MARIAGE,

Español

PARECE QUE LOS GITANOS Y GITANAS SOLAMENTE NACIERON EN EL MUNDO PARA SER LADRONES: NACEN DE PADRES LADRONES, CRÍANSE CON LADRONES, ESTUDIAN PARA LADRONES Y, FINALMENTE, SALEN CON SER LADRONES CORRIENTES Y MOLIENTES A TODO RUEDO; Y LA GANA DEL HURTAR Y EL HURTAR SON EN ELLOS COMO ACIDENTES INSEPARABLES, QUE NO SE QUITAN SINO CON LA MUERTE. UNA, PUES, DESTA NACIÓN, GITANA VIEJA, QUE PODÍA SER JUBILADA EN LA CIENCIA DE CACO, CRIÓ UNA MUCHACHA EN NOMBRE DE NIETA SUYA, A QUIEN PUSO NOMBRE PRECIOSA, Y A QUIEN ENSEÑÓ TODAS SUS GITANERÍAS Y MODOS DE EMBELECOS Y TRAZAS DE HURTAR. SALIÓ LA TAL PRECIOSA LA MÁS ÚNICA BAILADORA QUE SE HALLABA EN TODO EL GITANISMO, Y LA MÁS HERMOSA

Svenska

MEN FAR OCH MOR GINGO VISST INTE OCH LYCKÖNSKADE SIG TILL NÅGOT, UTAN I STÄLLET VORO DE GANSKA BEDRÖVADE. DE VORO ETT FATTIGT HUSMANSFOLK, OCH DERAS STÄLLE VAR INTE MYCKET STÖRRE ÄN EN TRÄDGÅRDSTÄPPA. DÅ DE FÖRST FLYTTADE DIT, KUNDE DÄR INTE FÖDAS MER ÄN EN GRIS OCH ETT PAR HÖNS, MEN DE VORO OVANLIGT STRÄVSAMMA OCH DUKTIGA MÄNNISKOR, OCH NU HADE DE BÅDE KOR OCH GÄSS. DET HADE GÅTT OFANTLIGT FRAMÅT FÖR DEM, OCH DE SKULLE HA VANDRAT MÖJDA OCH GLADA TILL KYRKAN DEN VACKRA MORGONEN, OM DE INTE HADE HAFT SONEN ATT TÄNKA PÅ. FAR KLAGADE ÖVER ATT HAN VAR TRÖG OCH LAT: INGENTING HADE HAN VELAT LÄRA I SKOLAN, OCH HAN VAR SÅ ODUGLIG, ATT MAN NÄTT OCH JÄMNT KUNDE SÄTTA HONOM TILL ATT VALLA GÄSS. OCH MOR NEKADE INTE

Deutsch

DER HERAUSGEBER VERSPRACH, SEIN BESTES ZU TUN FÜR DEN SCHRIFTSTELLERISCHEN KOLLEGEN. ETWAS VERWUNDERLICH WOLLT ES IHM NUN WOHL BEDÜNKEN, ALS SEIN FREUND IHM GESTAND, DAß DAS MANUSKRIPT VON EINEM KATER, MURR GEHEißEN, HERRÜHRE UND DESSEN LEBENSANSICHTEN ENTHALTE; DAS WORT WAR JEDOCH GEGEBEN, UND DA DER EINGANG DER HISTORIE IHM ZIEMLICH GUT STILISIERT SCHIEN, SO LIEF ER SOFORT, MIT DEM MANUSKRIPT IN DER TASCHE, ZU DEM HERRN DÜMMLER UNTER DEN LINDEN UND PROPONIERTE IHM DEN VERLAG DES KATERBUCHS. HERR DÜMMLER MEINTE, BIS JETZT HABE ER ZWAR NICHT UNTER SEINEN AUTOREN EINEN KATER GEHABT, WISSE AUCH NICHT, DAß IRGENDEINER SEINER WERTEN KOLLEGEN MIT EINEM MANN DES SCHLAGES

Українська

СИНИ ЙОГО ДУМАЛИ ІНШІ ДУМИ. АЛЕ ТРЕБА СПЕРШУ ТРОХИ БІЛЬШЕ РОЗПОВІСТИ ПРО ЙОГО СИНІВ. НА ДВАНАДЦЯТІМ РОЦІ ЇХ БУЛО ВІДДАНО ДО КИЇВСЬКОЇ АКАДЕМІЇ, БО ВСЯ ЗНАЧНА СТАРШИНА ВВАЖАЛА СВОЇМ НАЙПЕРШИМ ОБОВ'ЯЗКОМ ВІДДАВАТИ СВОЇХ ДІТЕЙ У НАУКУ, ХОЧ І РОБИЛОСЯ ЦЕ ЛИШЕ ЗАДЛЯ ТОГО, ЩОБ ОПІСЛЯ ЗОВСІМ ЇЇ ЗАБУТИ. БУЛИ ВОНИ ТОДІ, ЯК І ВСІ, ЩО ПОТРАПЛЯЛИ ДО БУРСИ, ДИКІ, ВИКОХАНІ НА ВОЛІ, І ТАМ ЇХ УЖЕ ПОТРОХУ ОБТІСУВАЛИ НА ОДИН КОПИЛ, ПІСЛЯ ЧОГО СТАВАЛИ ВОНИ ОДИН НА ОДНОГО СХОЖІ. СТАРШИЙ, ОСТАП, ПОЧАВ З ТОГО СВОЮ НАУКУ, ЩО ПЕРШОГО Ж РОКУ ВТІК ДОДОМУ. ЙОГО ПОВЕРНУЛИ, ТЯЖКО ВИПАРИЛИ Й ПОСАДОВИЛИ ЗА КНИЖКУ. ЧОТИРИ РАЗИ ЗАКОПУВАВ ВІН СВОГО БУКВАРЯ В ЗЕМЛЮ І ЧОТИРИ РАЗИ, ВІДШМАГАВШИ ЙОГО НЕМИЛОСЕРДНО, КУПУВАЛИ

Русский

ИТАК, ВСЕ МОИ БЛЕСТЯЩИЕ НАДЕЖДЫ РУШИЛИСЬ! ВМЕСТО ВЕСЕЛОЙ ПЕТЕРБУРГСКОЙ ЖИЗНИ ОЖИДАЛА МЕНЯ СКУКА В СТОРОНЕ ГЛУХОЙ И ОТДАЛЕННОЙ. СЛУЖБА, О КОТОРОЙ ЗА МИНУТУ ДУМАЛ Я С ТАКИМ ВОСТОРГОМ, ПОКАЗАЛАСЬ МНЕ ТЯЖКИМ НЕСЧАСТИЕМ. НО СПОРИТЬ БЫЛО НЕЧЕГО. НА ДРУГОЙ ДЕНЬ ПОУТРУ ПОДВЕЗЕНА БЫЛА К КРЫЛЬЦУ ДОРОЖНАЯ КИБИТКА; УЛОЖИЛИ В НЕЕ ЧЕМОДАН, ПОГРЕБЕЦ С ЧАЙНЫМ ПРИБОРОМ И УЗЛЫ С БУЛКАМИ И ПИРОГАМИ, ПОСЛЕДНИМИ ЗНАКАМИ ДОМАШНЕГО БАЛОВСТВА. РОДИТЕЛИ МОИ БЛАГОСЛОВИЛИ МЕНЯ. БАТЮШКА СКАЗАЛ МНЕ: «ПРОЩАЙ, ПЕТР. СЛУЖИ ВЕРНО, КОМУ ПРИСЯГНЕШЬ; СЛУШАЙСЯ НАЧАЛЬНИКОВ; ЗА ИХ ЛАСКОЙ НЕ ГОНЯЙСЯ; НА СЛУЖБУ НЕ НАПРАШИВАЙСЯ; ОТ СЛУЖБЫ НЕ ОТГОВАРИВАЙСЯ; И ПОМНИ ПОСЛОВИЦУ: БЕРЕГИ

Uppercase Latin	ABCDEFGHIJKLMNOPQRSTUVWXYZ
Lowercase Latin	ABCDEFGHIJKLMNOPQRSTUVWXYZ
Uppercase Cyrillic	АБВГДЕЁЖЗИЙКЛМНОПРСТУФХЦЧШЩЪЫЬЭЮЯ ҐЃЄЅІЇЈЉЊЌЎЏҐҒҚҢҮҲҺӘӨҰҲҴҶҸҔҘҖ ҊҘҮҰҲҶҸҔҘҖҊҒҢҺ
Lowercase Cyrillic	АБВГДЕЁЖЗИЙКЛМНОПРСТУФХЦЧШЩЪЫЬЭЮЯ ҐЃЄЅІЇЈЉЊЌЎЏҐҒҚҢҮҲҺӘӨҰҲҴҶҸҔҘҖҊҘҮҰҲҶҸҔҘҖҊҒҢҺ ҊҒҢҺӘӨҰҲҴҶҸҔҘҖ
Accented Latin Uppercase	ÀÁÂÃÄÅĀĂĄǍǞǠǺĆĈĊČĎÈÉÊËĒĔĖĘĚĒĞĜĠĢĤÌÍÎÏĨĬĮĬĴĶĹĻĽĿŁÑŃŅŇÒÓÔÕ ÖŌŎŐŘŘŚŜŞŠŠŢŤŦŢÙÚÛÜŨŪŬŮŰŲŲŴẀẄẄẄÝŶŸỲỸŹŽŽÆǼǢÐØǾÞĲĴĴ ĴDZĴDŽNJLJŒIJƏ
Accented Lowercase	àáâãäåāăąǎǟǡǻćĉċčďèéêëēĕėęěēğĝġĝĥìíîïĩĭĭĭ

	Deactivated	Activated
Proportional Lining	$23 €56	$23 €56
Superscript & Subscript	H123H123	$H^{123}H_{123}$
Numenator & Denumenator	H123H123	$H^{123}H_{123}$
Fractions	1/2 1/3 2/3 1/4 3/4	½ ⅓ ⅔ ¼ ¾
Stylistic Sets		Beacon On
		Beacon Of
		Solid Figures
		Black Circled Figures
		Circled Figures
		Alternates

Supported languages: Afrikaans, Azeri (cyr), Azeri (lat), Bashkir, Belarusian, Bulgarian, Catalan, Chechen, Chuvash, Czech, Danish, Dutch, English, Esperanto, Estonian, Finnish, French, Gaelic (Irish), Galician, German, Hungarian, Icelandic, Ingush, Italian, Kazakh, Kurdish (lat), Kyrghiz, Latvian, Lithuanian, Moldavian (cyr), Mongolian (cyr), Mongolian (lat), Norwegian, Polish, Portuguese, Romanian, Russian, Serbian, Slovene, Spanish, Swedish, Tadzhik, Tatar, Turkish, Turkmen, Ukrainian, Uzbek (Cyr), Uzbek (lat), and others

Designer:
Schrift Foundry started from more than a decade of experience in typography and publishing at Schrift Publishers, founded by Eugene Yukechev and Rustam Gabbasov in 2013. Over the years, Schrift Publishers released dozens of publications on typography and the art of type. Among their notable book releases are monographs on Solomon Telingater, Vladimir Favorsky, Adrian Frutiger, Villu Toots, and a translation of Eric Gill's "An Essay on Typography".
In 2020, Schrift Foundry was established with the arrival of Dmitry Pilikov, marking a new phase in their work and bringing a more focused, systematic approach to type production. By now, the foundry offered a diverse collection of fonts and provided custom type production for a wide range of customers. Their typefaces are designed to balance form and function, whether for book layouts or large-scale media projects.
Schrift Foundry approaches typography as both an art and a craft. Their designs reflect a curiosity of how people engage with text, resulting in fonts that are not only visually appealing but also practical and reliable across different contexts.
Eugene Yukechev obtained a degree in philology and graduated from the British Higher School of Art and Design's Type and Typography programme. He pursued further education at the Plantin Institute of Typography in Antwerp. In 2013, he founded Schrift Publishers, a publishing house with an extensive editorial programme and an online periodical called Type Journal. In 2024, together with partners from Schrift Publishers, Eugene launched a type design studio, the Schrift Foundry.
Dmitry Pilikov is a designer and art director specializing in maps, navigation systems, product design, and consulting for start-ups. Dmitry is a co-founder of Schrift Foundry. He graduated from Novosibirsk State Technical University and participated in Designworkout workshops led by Dima Barbanel. He has organized design conferences while developing comprehensive corporate design programs. Dmitry frequently shares his expertise with teams and collaborates with renowned type foundries, including Swiss Typefaces and Our Type, to customize typefaces for specific projects.

Contact: info@type.today, http://type.today
© 2024. type.today All rights reserved. This file may be used for evaluation purposes only.